Übersichtskarten

zum La-Bereich Mitte

Gültig ab 15.12.2024

Übersichtskarte zur La Mitte

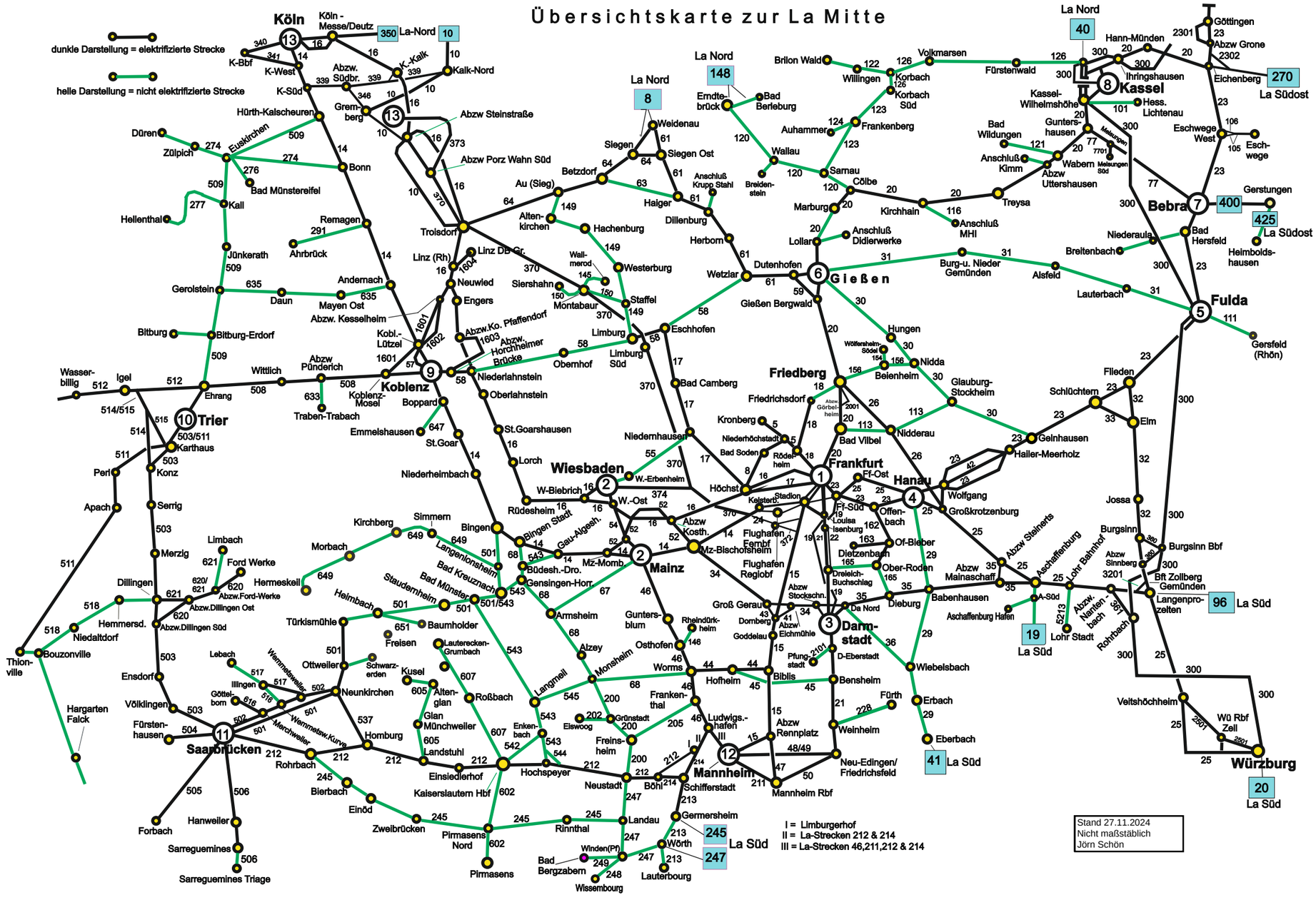

Frankfurt am Main 1

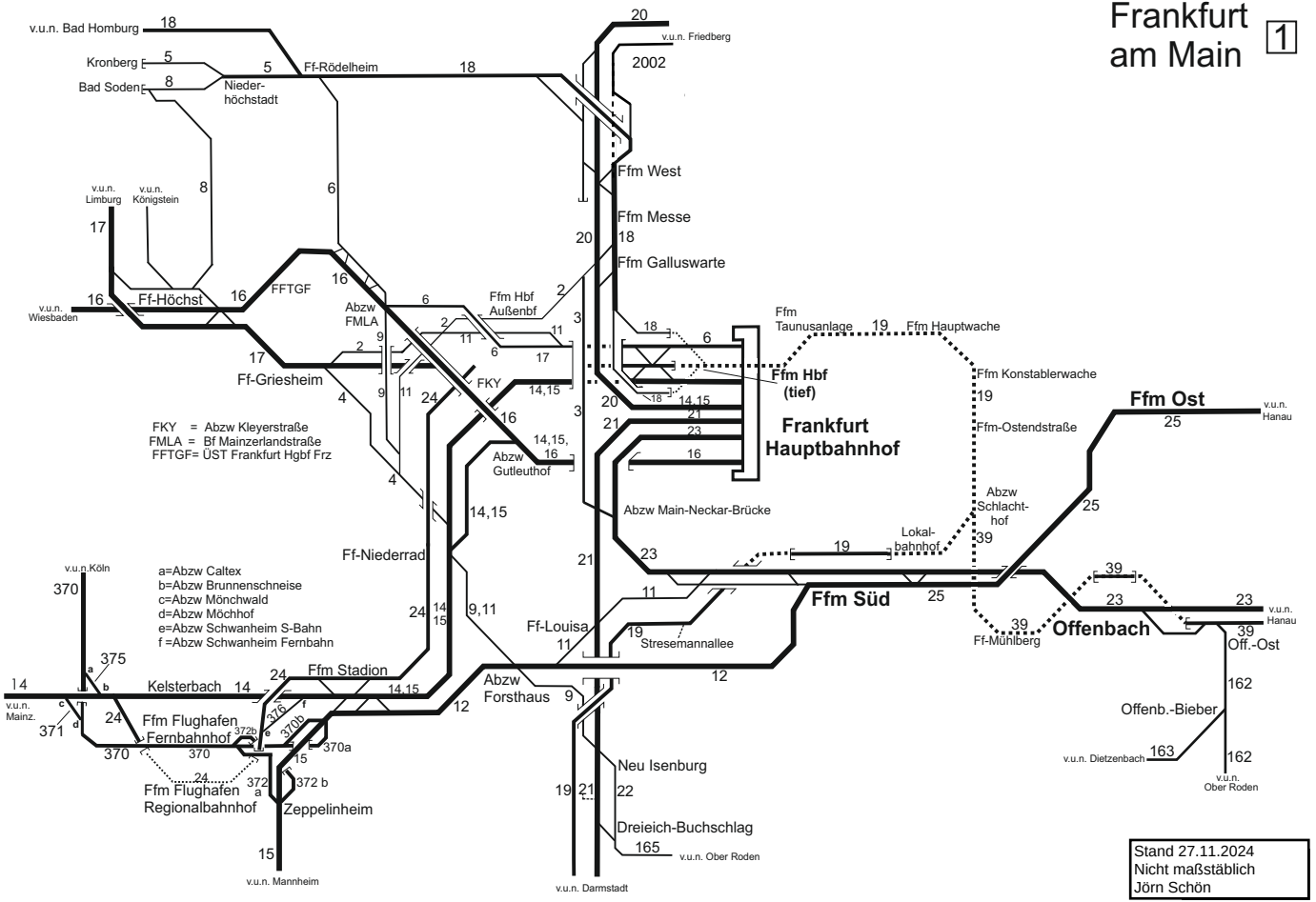

Stand 27.11.2024
Nicht maßstäblich
Jörn Schön

zur Übersichtskarte

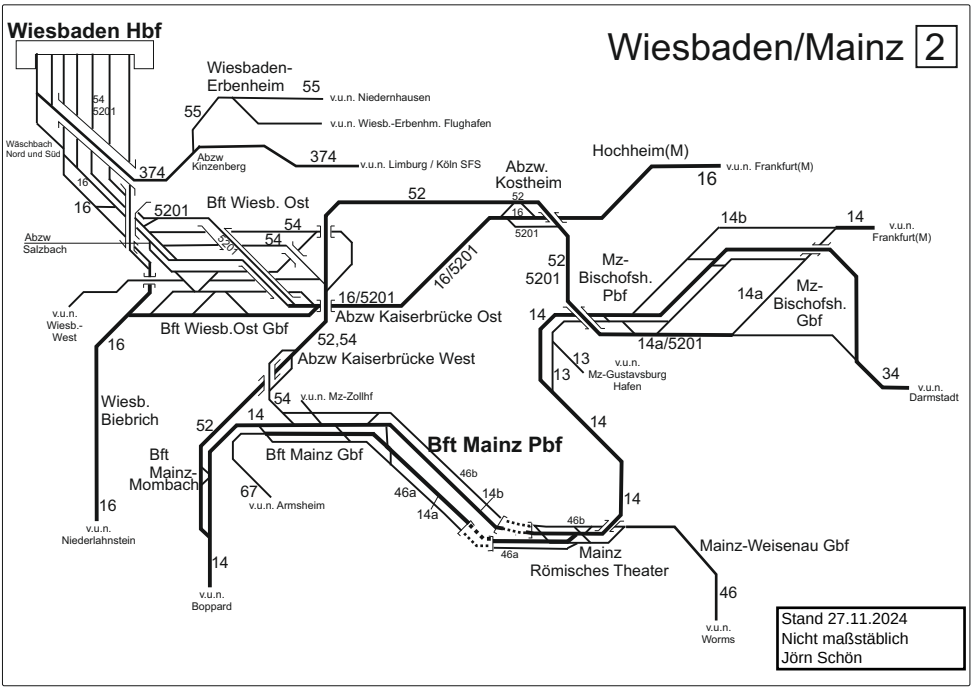

zur Übersichtskarte

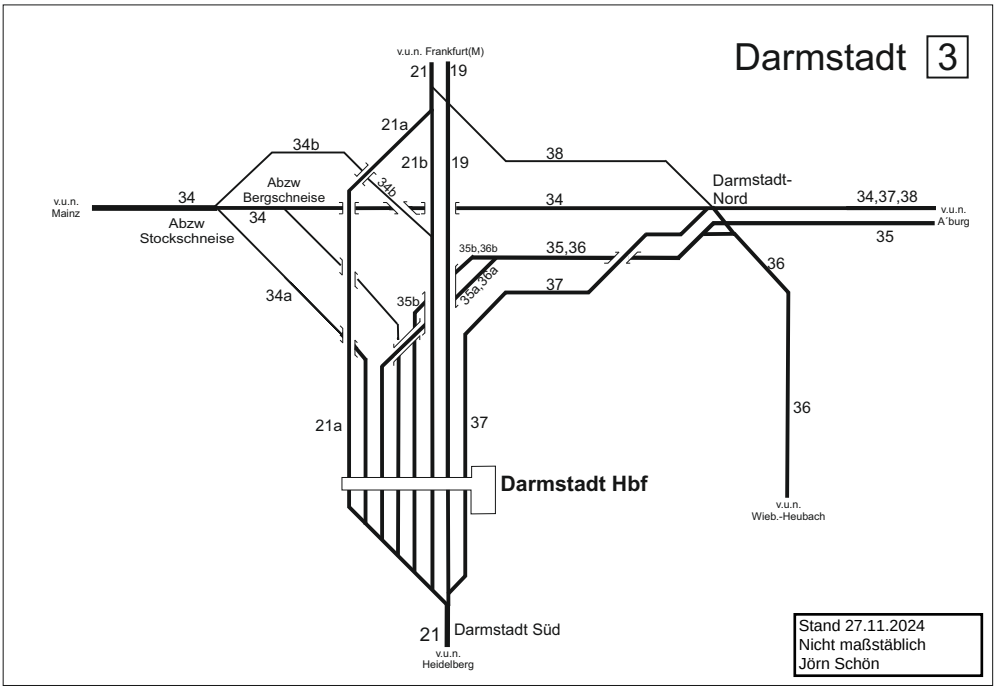

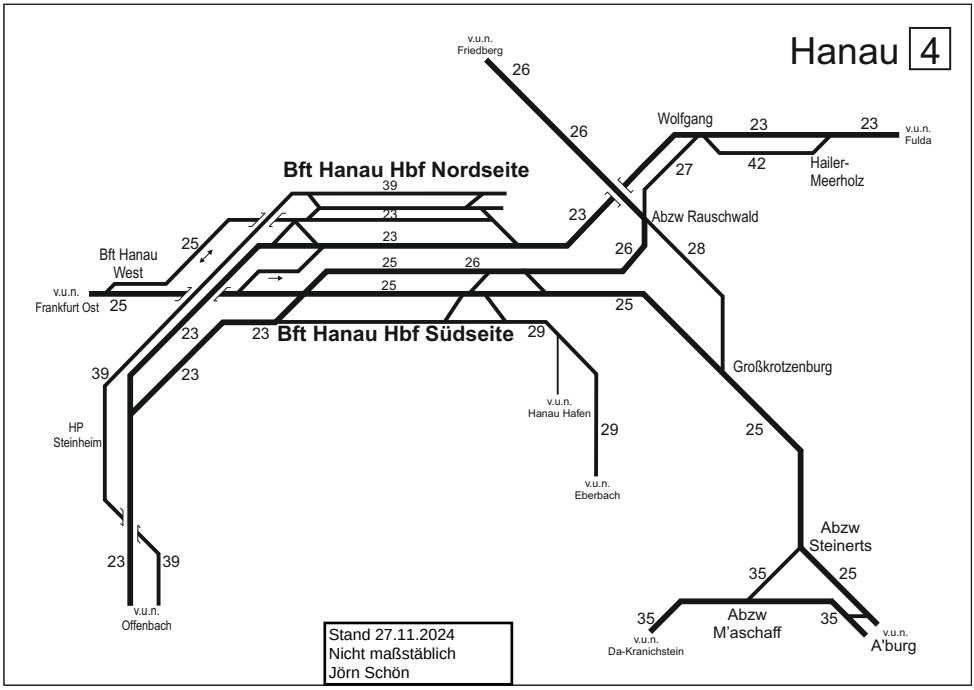

zur Übersichtskarte

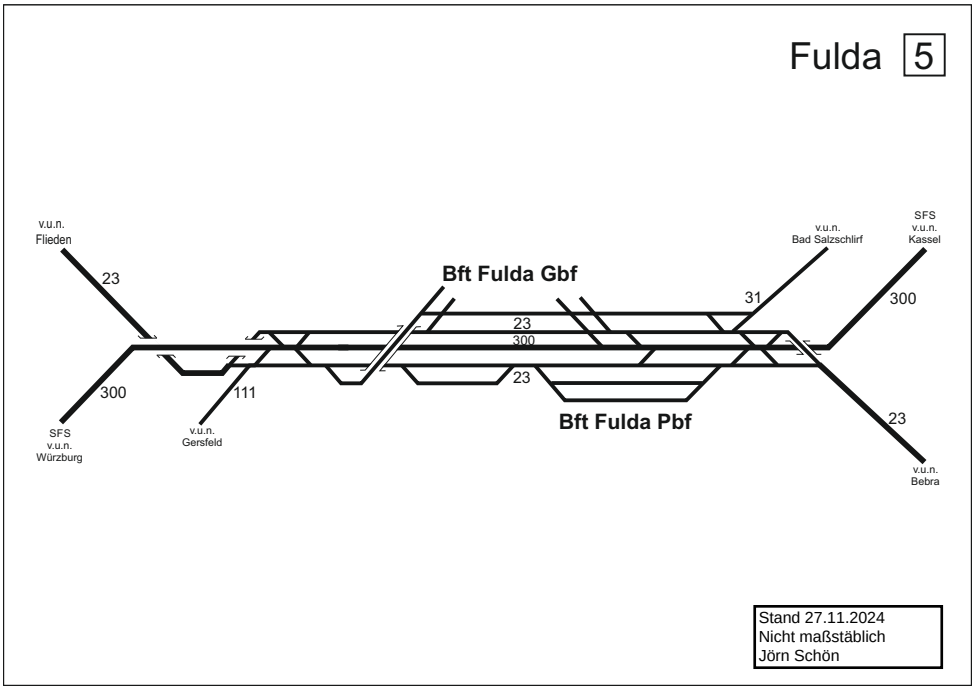

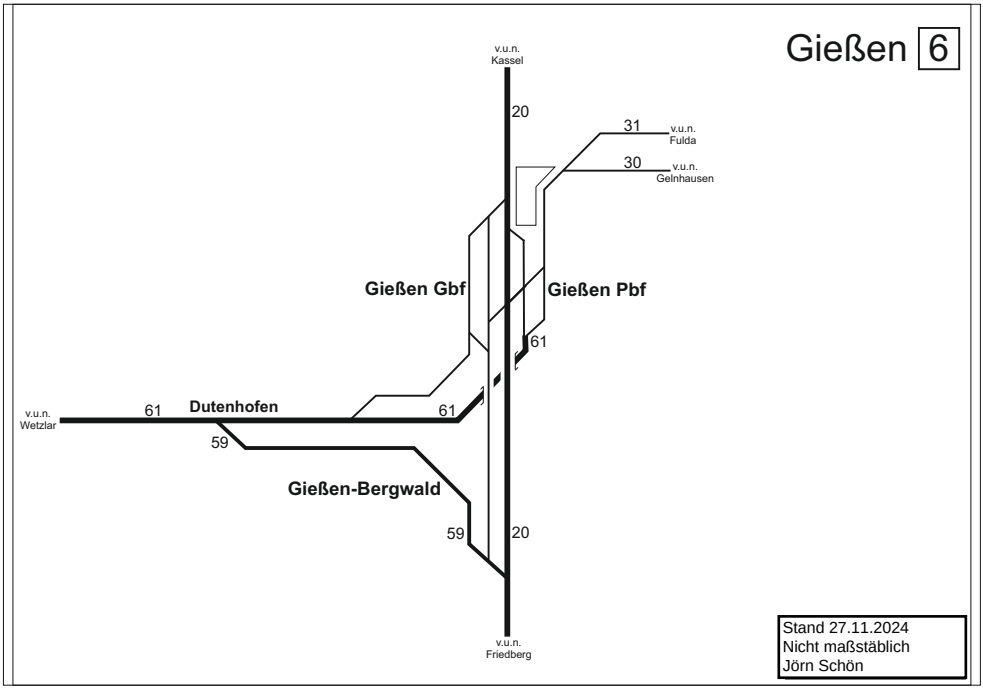

zur Übersichtskarte

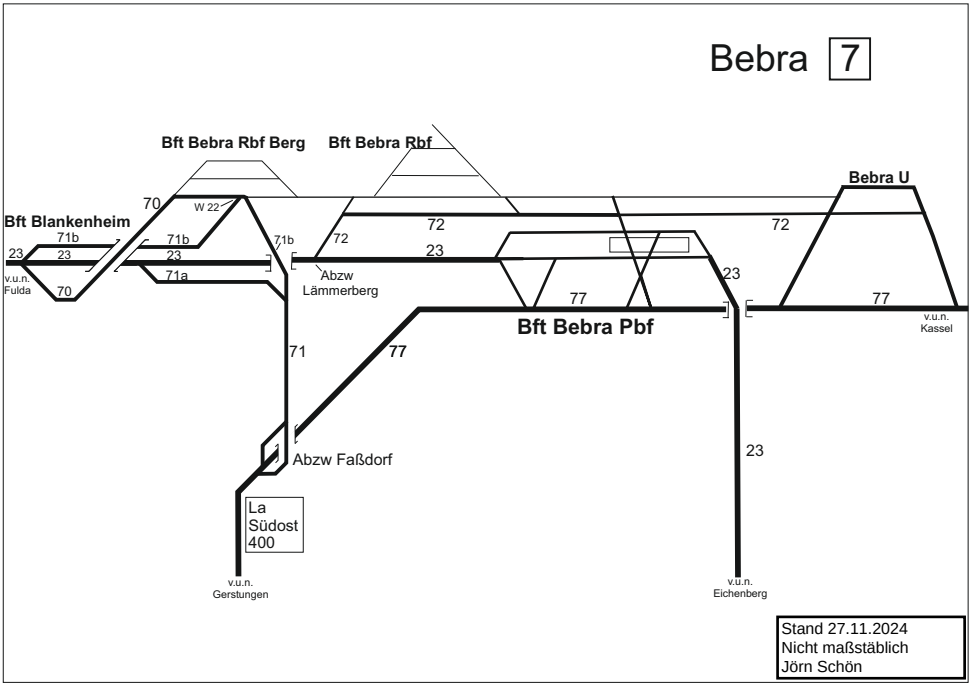

Kassel 8

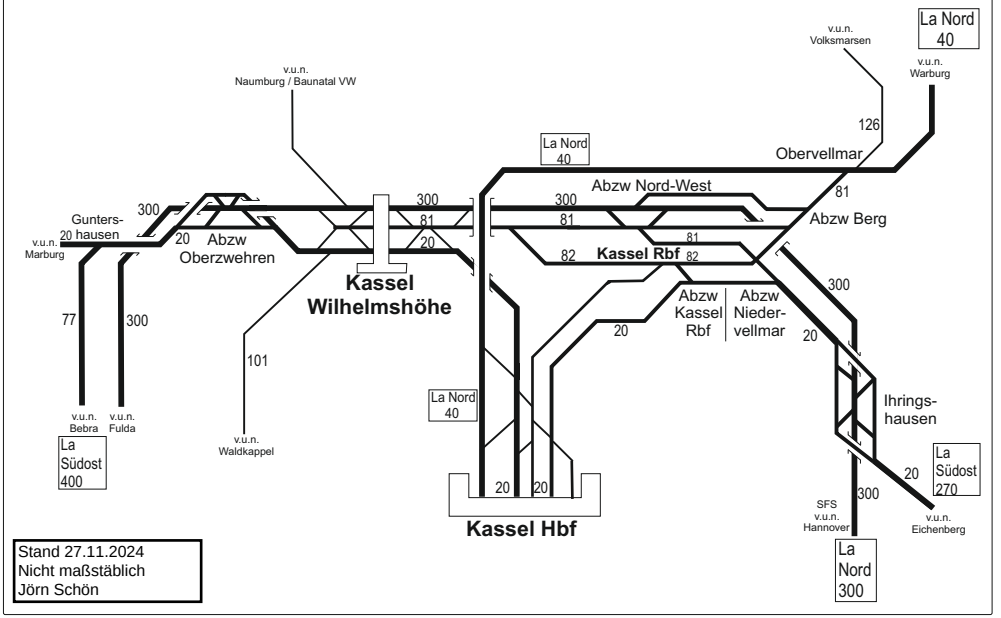

zur Übersichtskarte

Koblenz 9

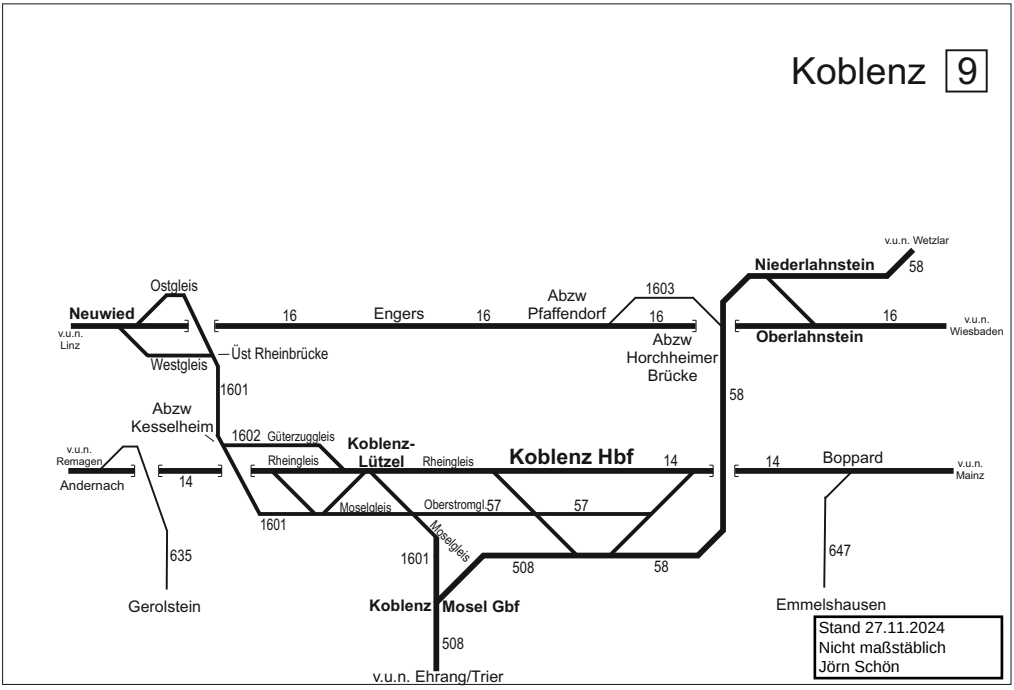

Trier/Ehrang 10

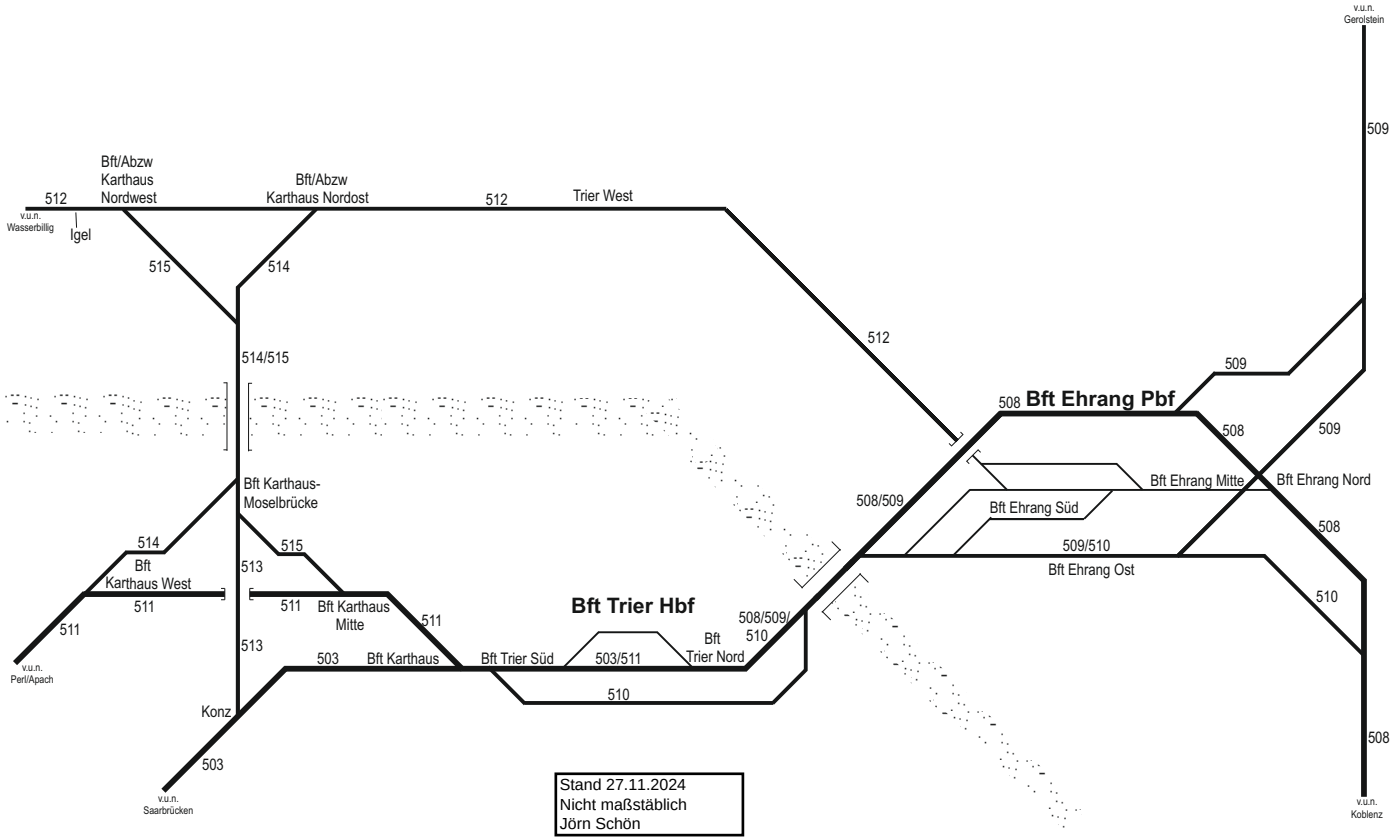

Stand 27.11.2024
Nicht maßstäblich
Jörn Schön

zur Übersichtskarte

Saarbrücken

11

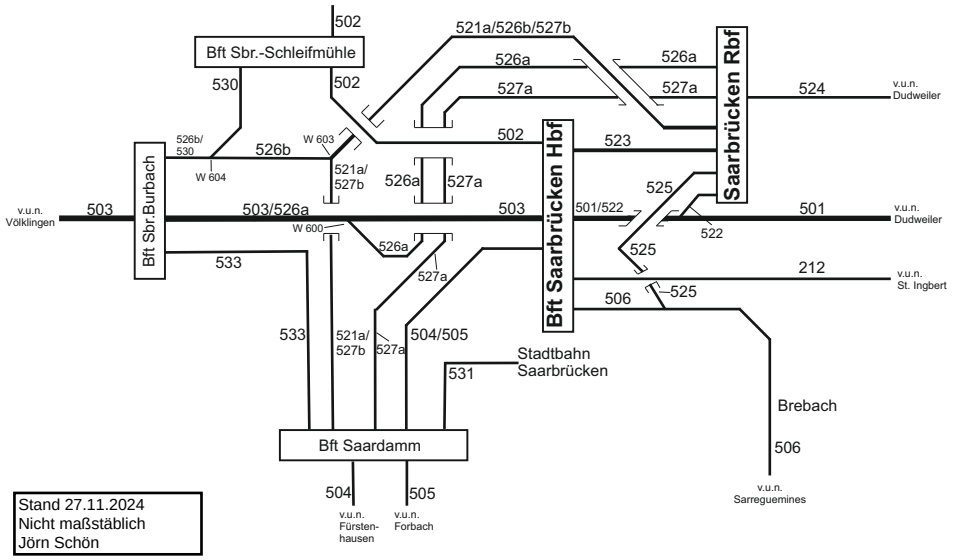

Stand 27.11.2024
Nicht maßstäblich
Jörn Schön

zur Übersichtskarte

Ludwigshafen (Rh) - Mannheim - Heidelberg

12

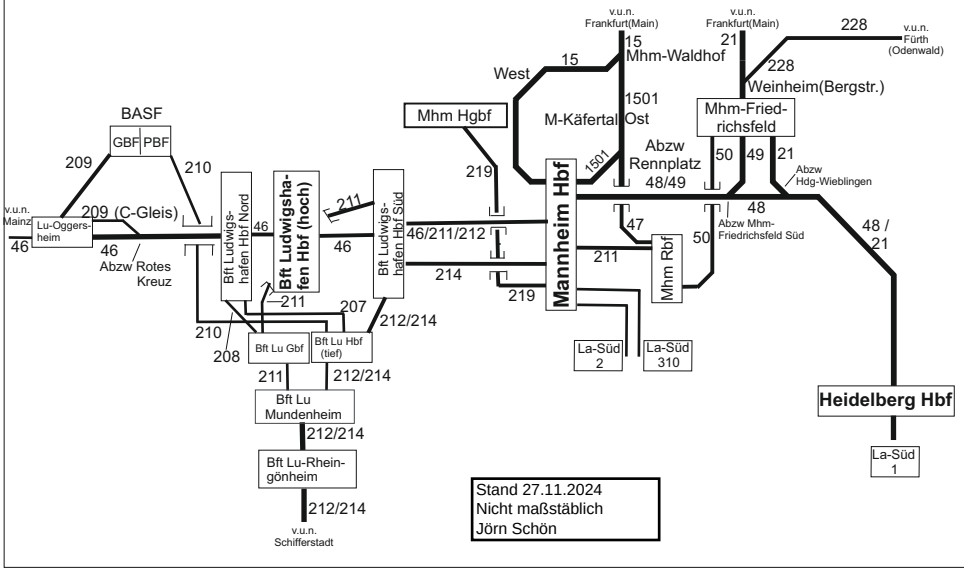

Stand 27.11.2024
Nicht maßstäblich
Jörn Schön

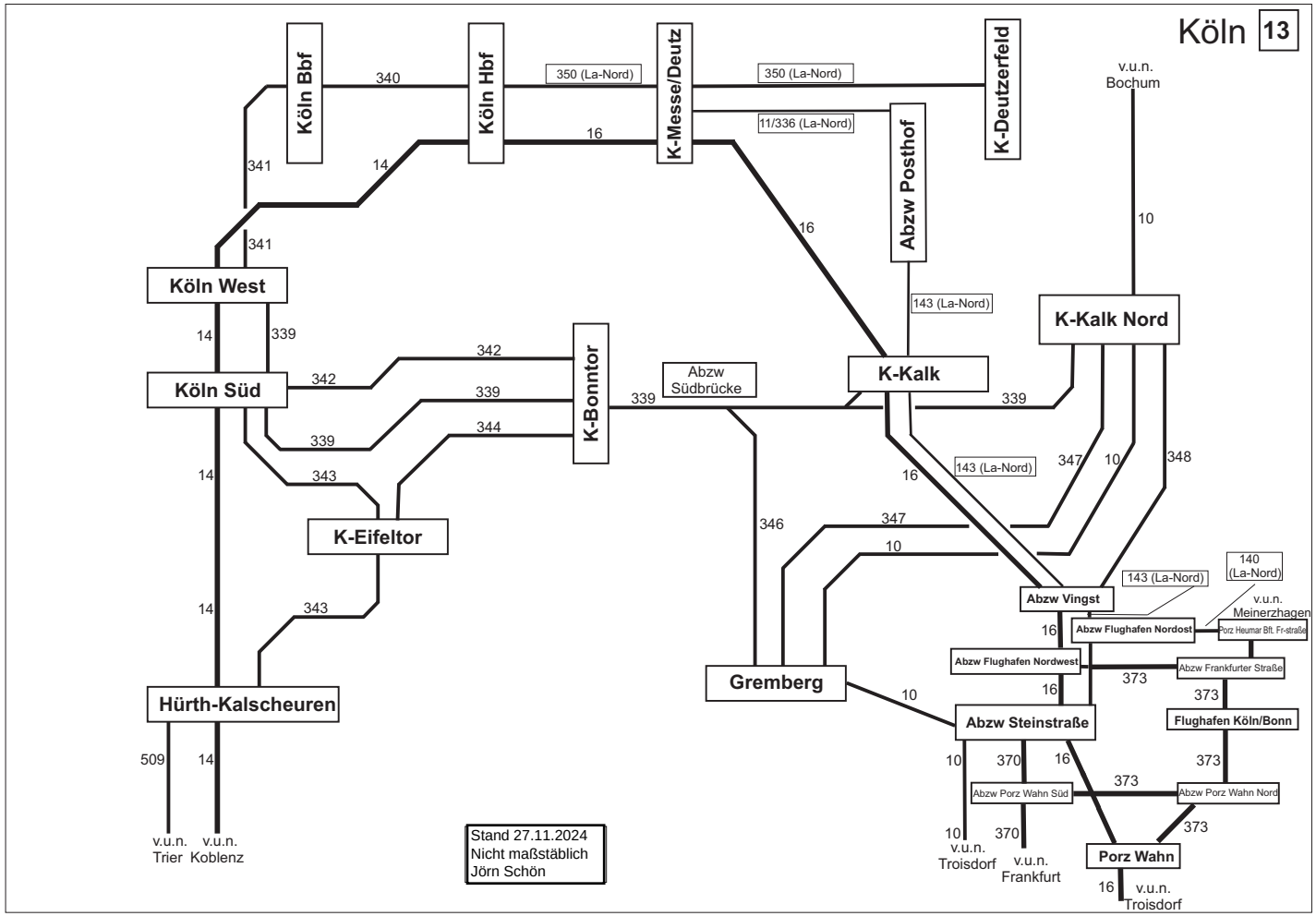

zur Übersichtskarte

Übersichtskarten

zum La-Bereich Nord

Gültig ab: 15.12.2024

Übersichtskarte A zur La -Bereich Nord-

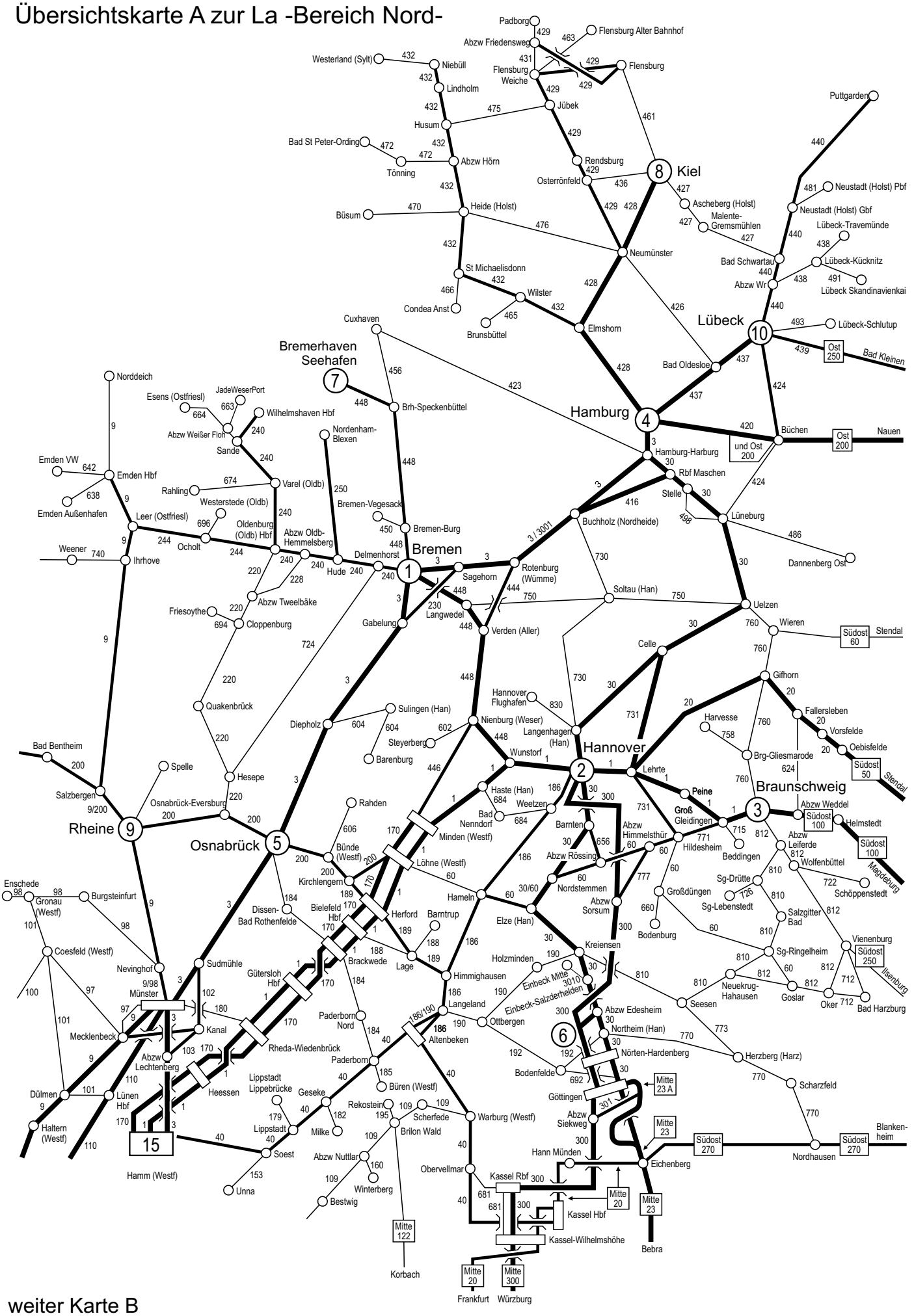

weiter Karte B

Übersichtskarte B
zur La-Bereich Nord-

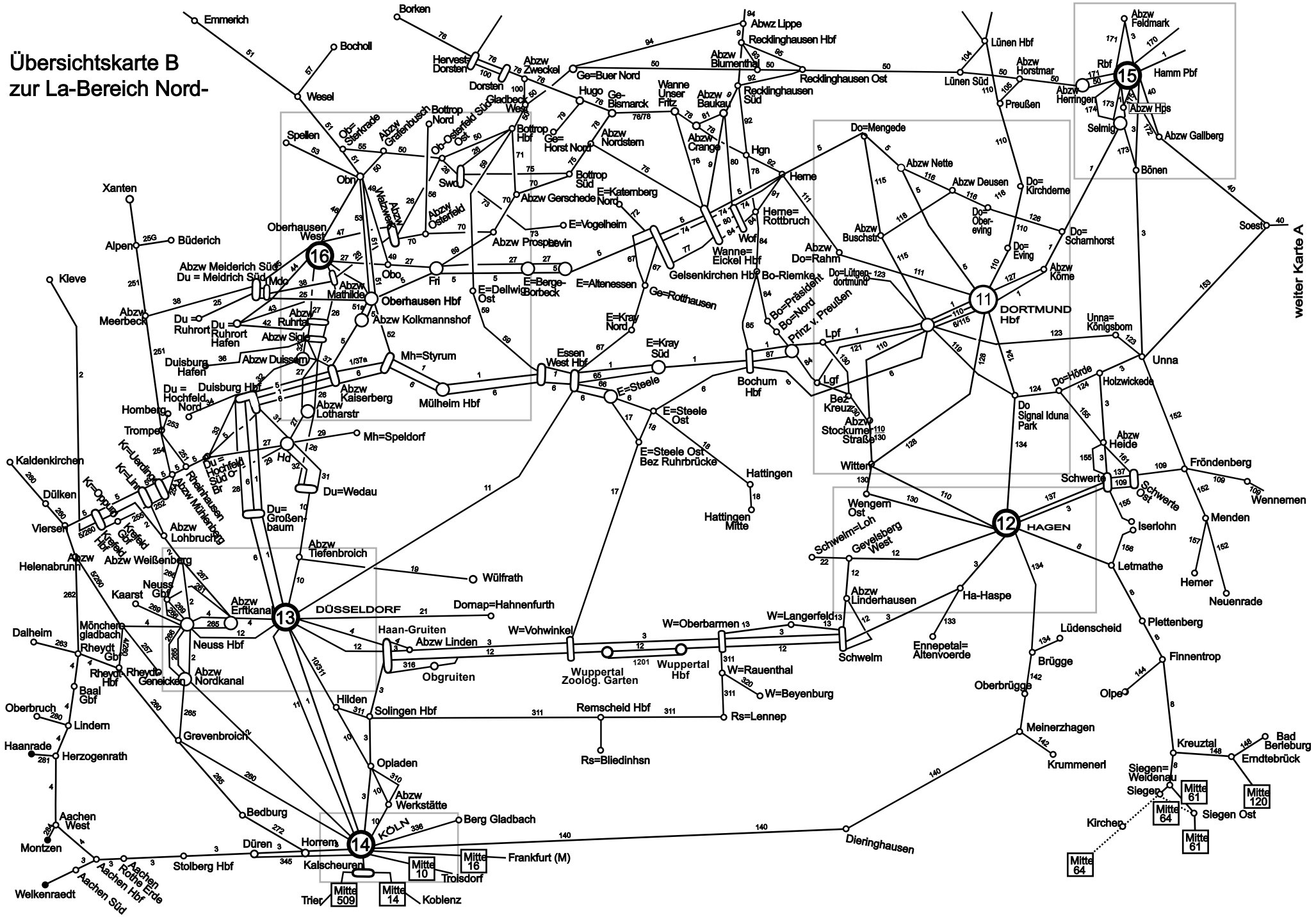

Nebenkarten zu den Übersichtskarten - La Bereich Nord

1

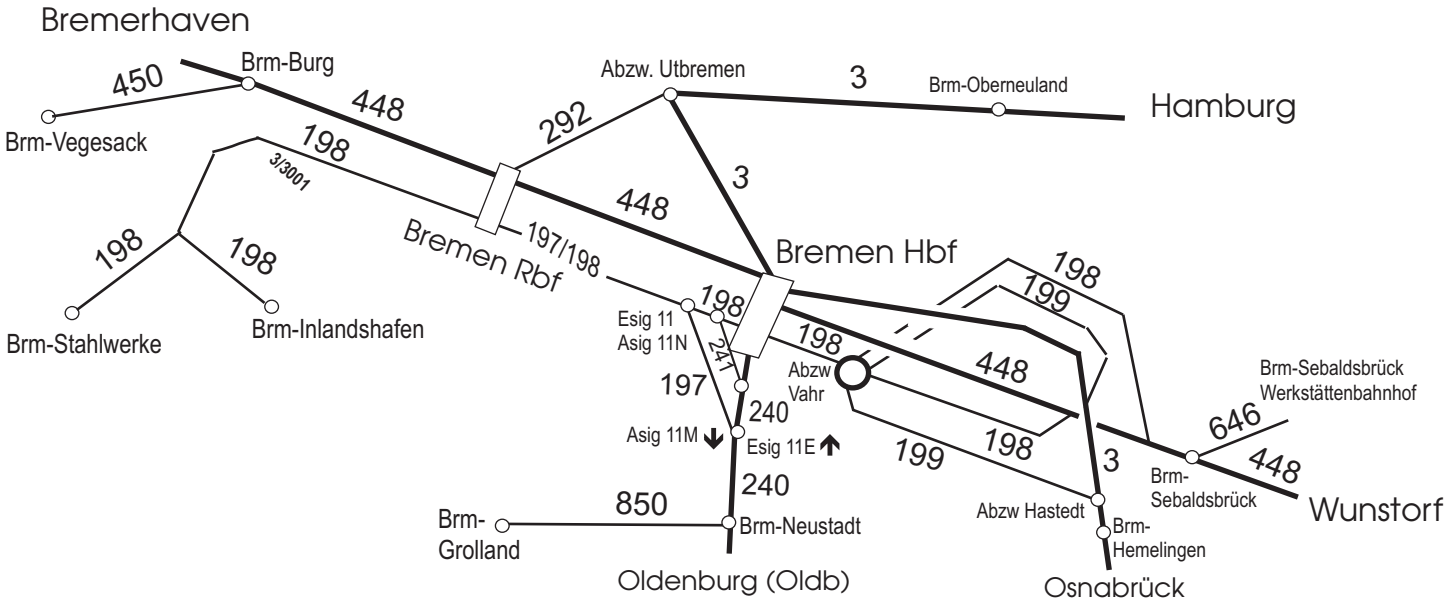

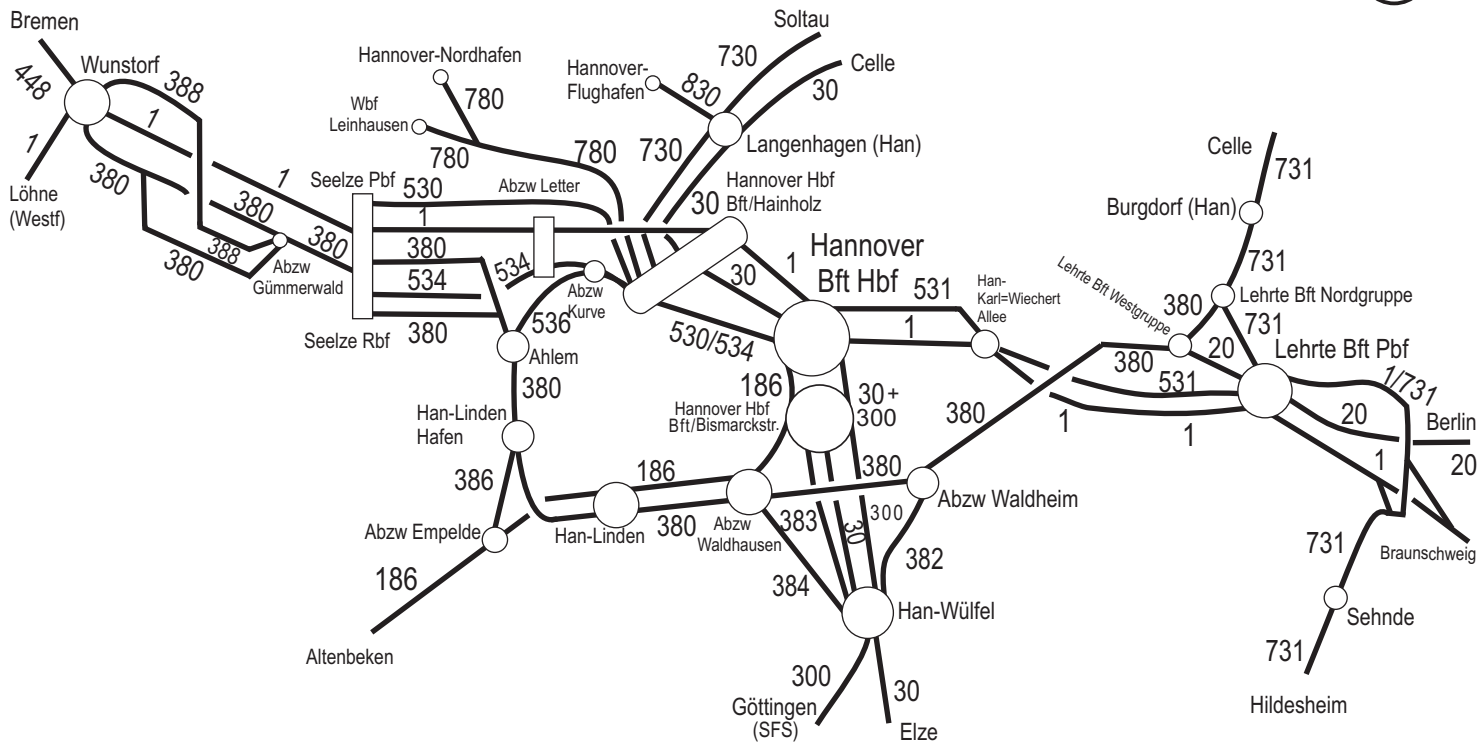
Bremen
448
Wunstorf
388
1
1
Löhne
(Westf)
380
1
380
380
388
380
Abzw
Gümmerwald
Seelze Pbf
530
1
380
534
Seelze Rbf
380
Hannover-Nordhafen
780
Wbf
Leinhausen
780
780
Abzw Letter
534A
Abzw
Kurve
536
Ahlem
380
Han-Linden
Hafen
386
Abzw Empelde
186
Altenbeken
Hannover-
Flughafen
830
730
730
Soltau
Celle
30
Langenhagen (Han)
30
Hannover Hbf
Bft/Hainholz
Hannover
Bft Hbf
1
30
530/534
186
Hannover Hbf
Bft/Bismarckstr.
30+
300
531
1
Han-
Karl=Wiechert
Allee
380
Abzw Waldheim
186
Han-Linden
380
Abzw
Waldhausen
383
30
300
382
384
Han-Wülfel
300
Göttingen
(SFS)
30
Elze
Lehrte Bft Westgruppe
380
1
1
Celle
731
Burgdorf (Han)
731
380
Lehrte Bft Nordgruppe
731
20
Lehrte Bft Pbf
1/731
20
Berlin
1
20
Braunschweig
731
Sehnde
731
Hildesheim

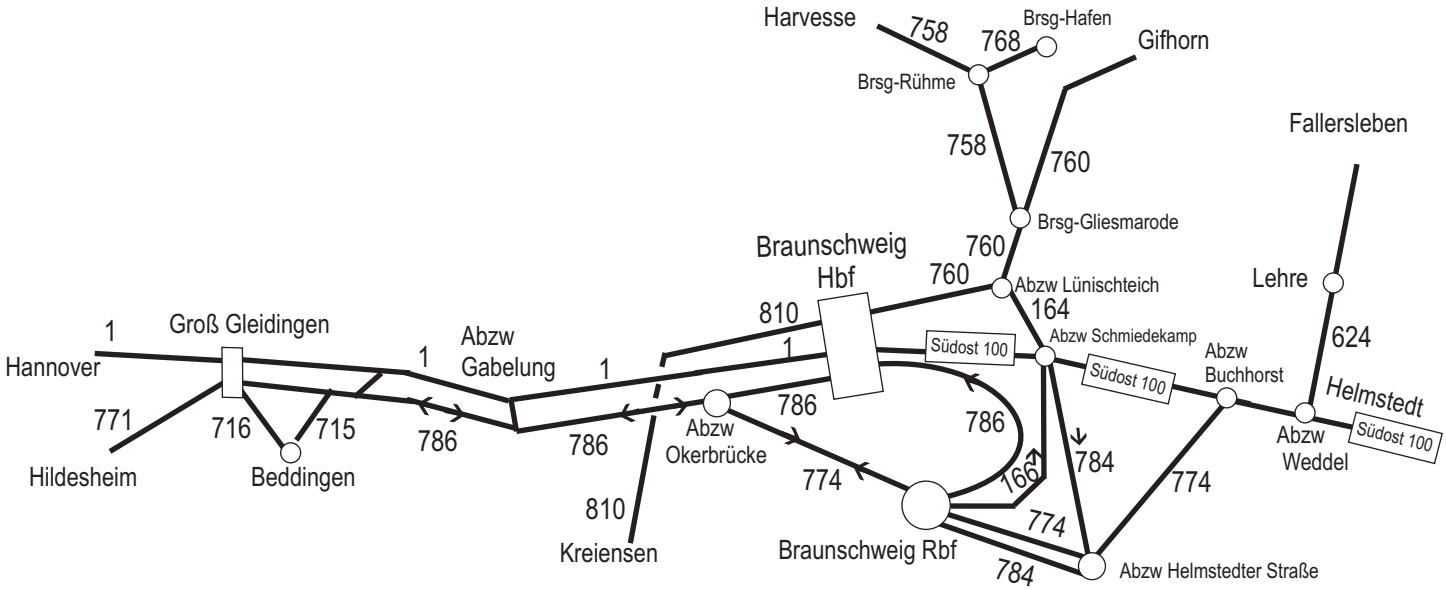
Harvesse
758
768
Brsg-Hafen
Gifhorn
Brsg-Rühme
758
760
Fallersleben
Brsg-Gliesmarode
Braunschweig
Hbf
760
760
Abzw Lünischteich
164
Lehre
810
1
Groß Gleidingen
Abzw
Gabelung
1
1
1
Abzw Schmiedekamp
Abzw
Buchhorst
624
Hannover
Südost 100
Südost 100
Helmstedt
771
716
715
786
786
786
786
Abzw
Okerbrücke
Abzw
Weddel
Südost 100
Hildesheim
Beddingen
774
166
784
774
810
774
Kreiensen
Braunschweig Rbf
784
Abzw Helmstedter Straße

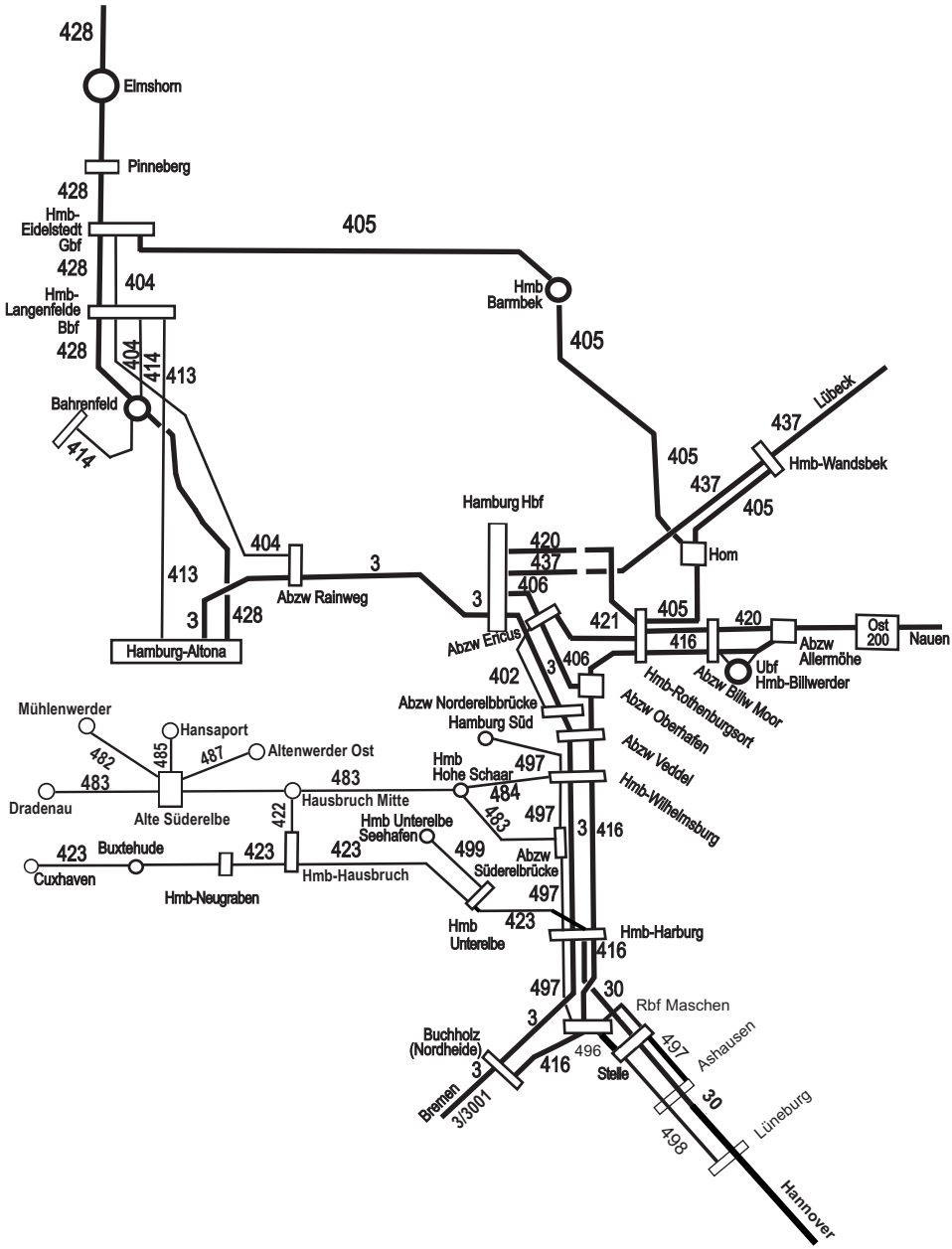
428
Elmshorn
Pinneberg
428
Hmb-
Eidelstedt
Gbf
405
428
404
Hmb-
Langenfelde
Bbf
Hmb
Barmbek
428
404
414
413
405
Bahrenfeld
414
Lübeck
437
405
Hmb-Wandsbek
437
405
Hamburg Hbf
Hom
404
420
437
3
406
413
Abzw Rainweg
3
3
428
421
405
420
416
Ost
200
Nauen
Hamburg-Altona
Abzw Ericus
Abzw
Allermöhe
402
3
406
Ubf
Hmb-Billwerder
Hmb-Rothenburgsort
Abzw Billw Moor
Abzw Oberhafen
Abzw Norderelbbrücke
Hamburg Süd
Mühlenwerder
Hansaport
482
485
487
Altenwerder Ost
Abzw Veddel
Hmb
Hohe Schaar
497
483
484
Hmb-Wilhelmsburg
483
Dradenau
Alte Süderelbe
Hausbruch Mitte
422
483
497
Hmb Unterelbe
Seehafen
3
416
423
Buxtehude
423
423
499
Abzw
Süderelbrücke
Cuxhaven
Hmb-Neugraben
Hmb-Hausbruch
497
423
Hmb
Unterelbe
Hmb-Harburg
416
497
30
Rbf Maschen
3
Buchholz
(Nordheide)
496
497
Ashausen
3
416
Stelle
30
Bremen
3/3001
Lüneburg
498
Hannover

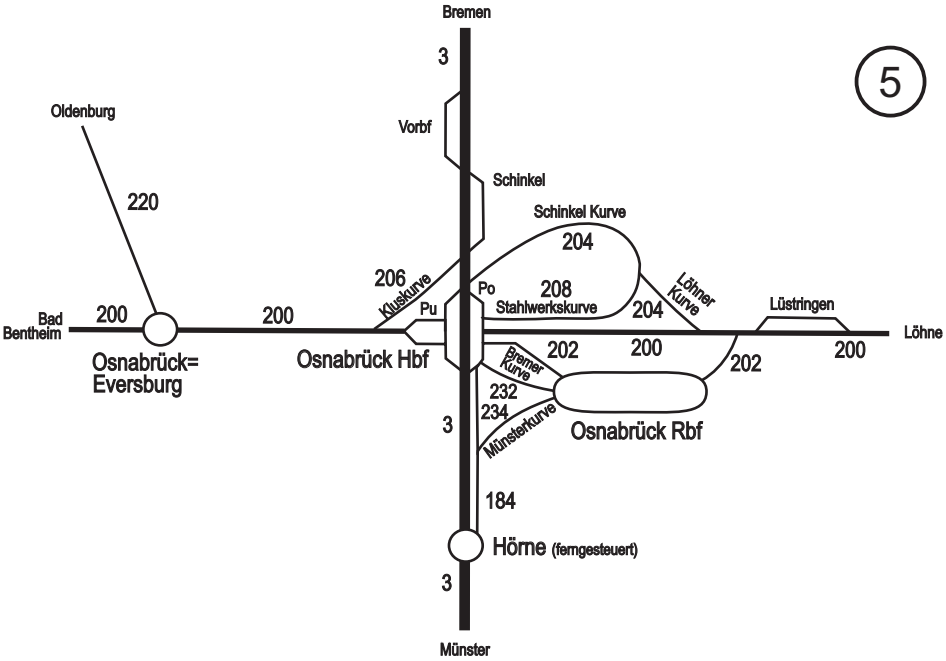
5
Bremen
3
Vorbf
Schinkel
Schinkel Kurve
204
Oldenburg
220
206
Kluskurve
Po
208
Löhner Kurve
Bad Bentheim
200
200
Pu
Stahlwerkskurve
204
Lüstringen
Löhne
Osnabrück= Eversburg
Osnabrück Hbf
202
200
202
200
Bremer Kurve
232
234
Münsterkurve
3
Osnabrück Rbf
184
Hörne (ferngesteuert)
3
Münster

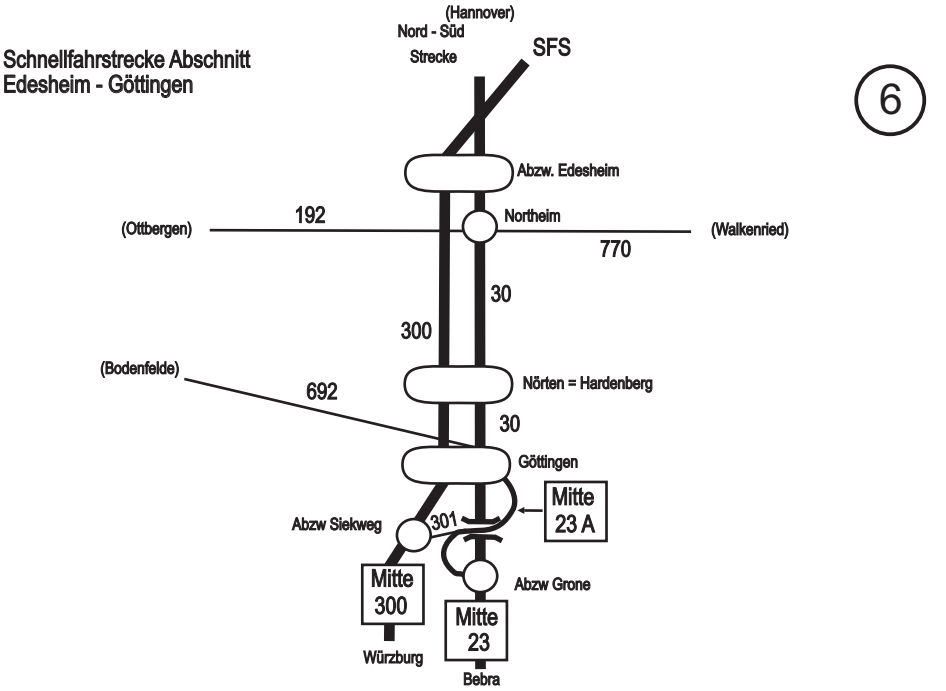
Schnellfahrstrecke Abschnitt
Edesheim - Göttingen
6
(Hannover)
Nord - Süd
Strecke
SFS
Abzw. Edesheim
(Ottbergen)
192
Northeim
(Walkenried)
770
30
300
(Bodenfelde)
692
Nörten = Hardenberg
30
Göttingen
Mitte
23 A
Abzw Siekweg
301
Abzw Grone
Mitte
300
Mitte
23
Würzburg
Bebra

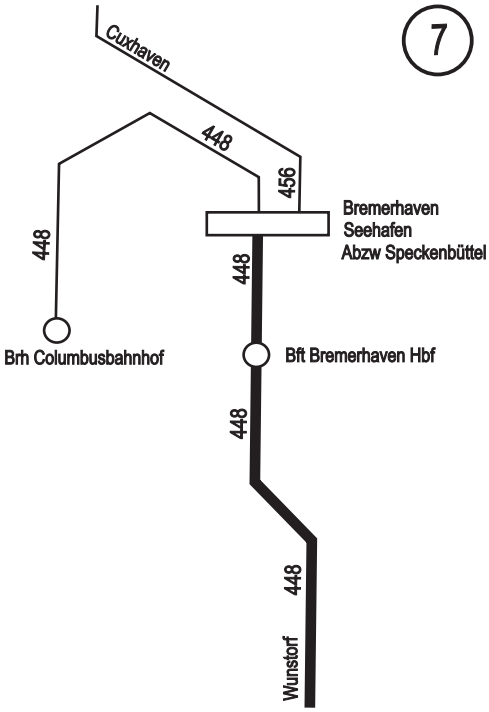
7
Cuxhaven
448
456
448
Bremerhaven
Seehafen
Abzw Speckenbüttel
448
Brh Columbusbahnhof
Bft Bremerhaven Hbf
448
448
Wunstorf

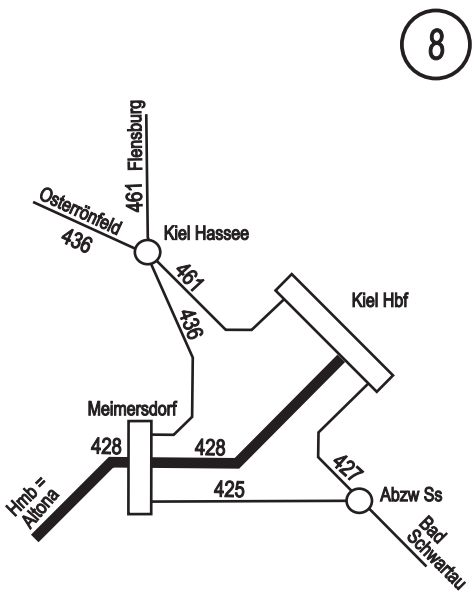
8
Flensburg
461
Osterrönfeld
436
Kiel Hassee
461
436
Kiel Hbf
Meimersdorf
428
428
427
Hmb = Altona
425
Abzw Ss
Bad Schwartau

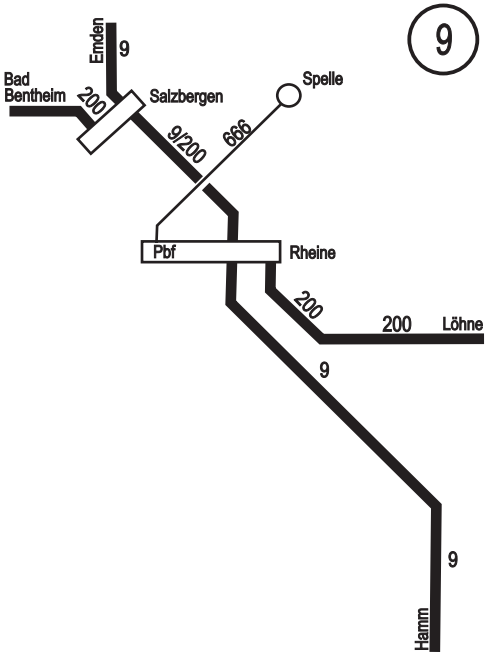
9
Emden
9
Bad Bentheim
200
Salzbergen
Spelle
9/200
666
Pbf
Rheine
200
200
Löhne
9
9
Hamm

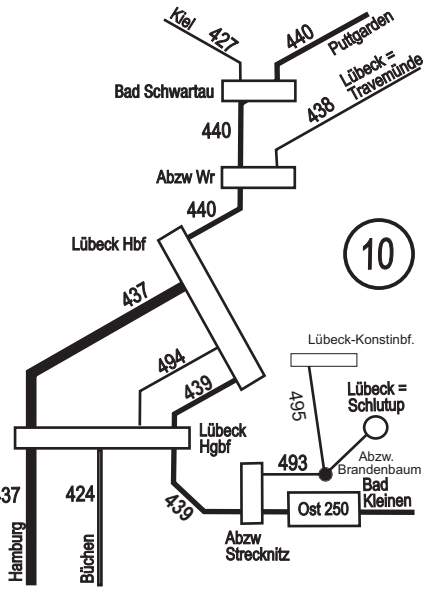
Kiel
427
440
Puttgarden
Lübeck = Travemünde
Bad Schwartau
438
440
Abzw Wr
440
Lübeck Hbf
10
437
Lübeck-Konstinbf.
494
439
495
Lübeck = Schlutup
Lübeck Hgbf
493
Abzw. Brandenbaum
Bad Kleinen
437
424
439
Ost 250
Abzw Strecknitz
Hamburg
Büchen

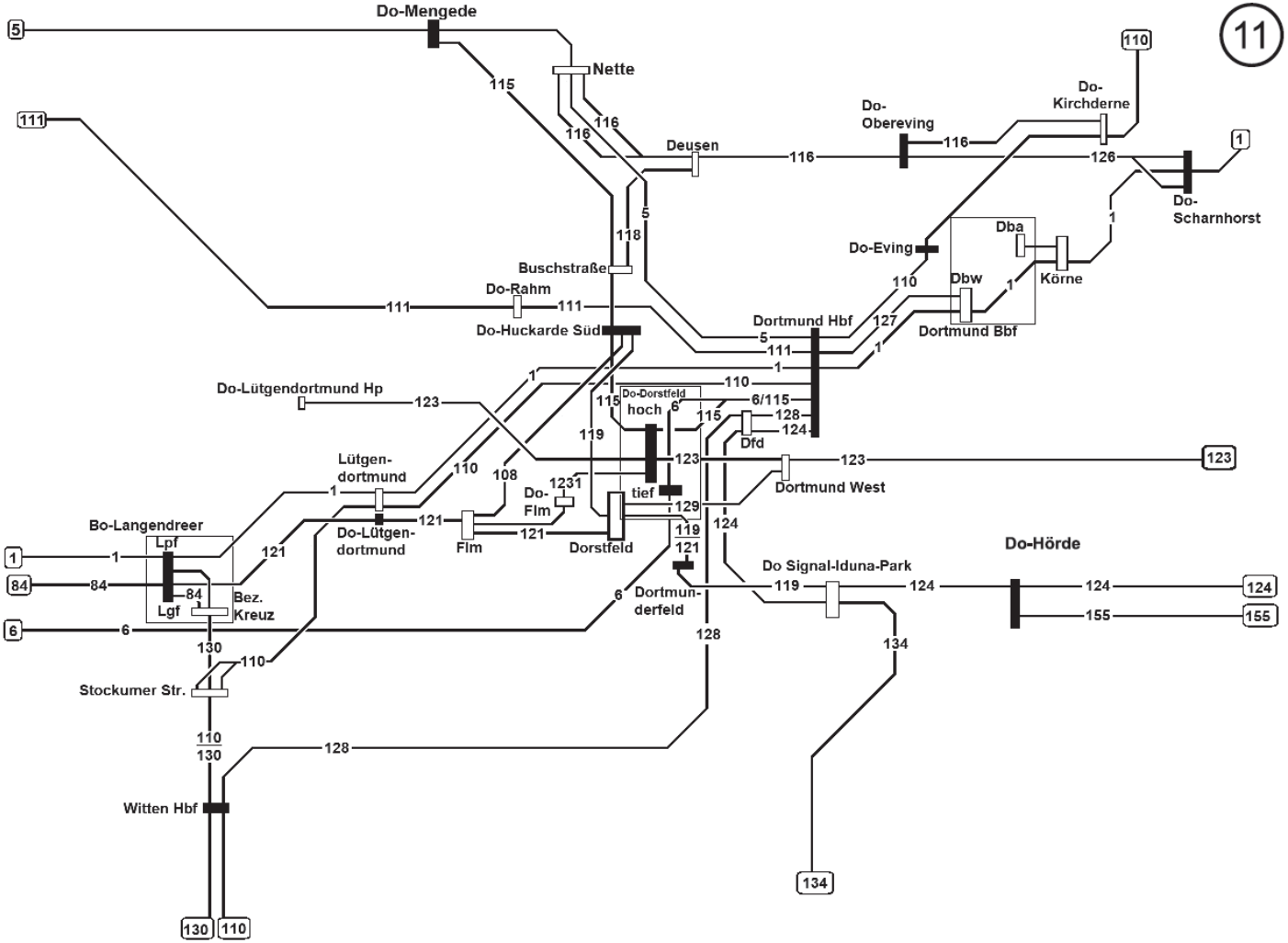
11
Do-Mengede
Nette
Deusen
Do-Obereving
Do-Kirchderne
Do-Scharnhorst
Do-Eving
Dba
Dbw
Körne
Dortmund Bbf
Dortmund Hbf
Buschstraße
Do-Rahm
Do-Huckarde Süd
Do-Lütgendortmund Hp
Do-Dorstfeld
hoch
tief
Dfd
Dortmund West
Lütgen-
dortmund
Do-Flm
Flm
Do-Lütgen-
dortmund
Dorstfeld
Dortmun-
derfeld
Bo-Langendreer
Lpf
Lgf
Bez.
Kreuz
Do-Hörde
Do Signal-Iduna-Park
Stockumer Str.
Witten Hbf

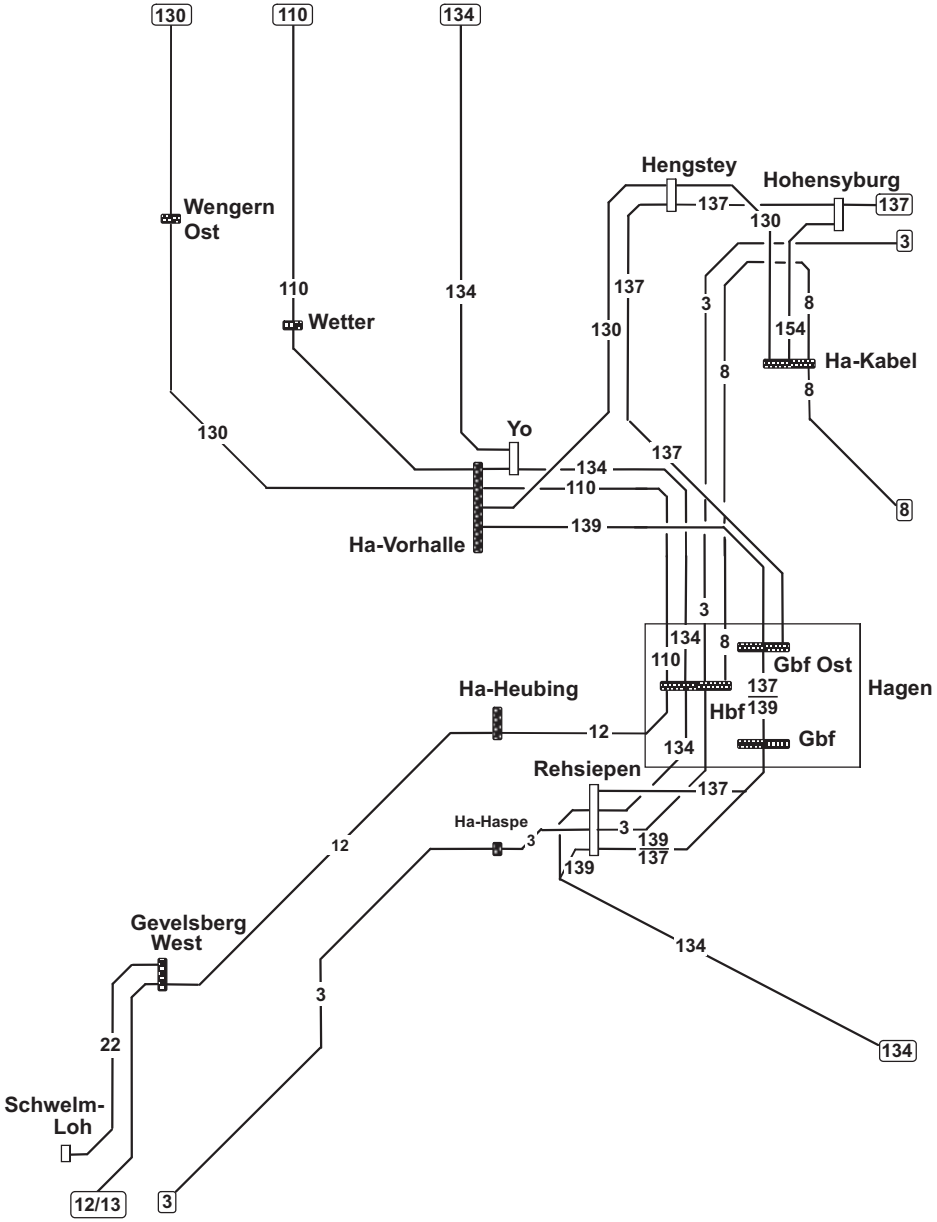
130
110
134
Wengern Ost
Wetter
Hengstey
Hohensyburg
137
130
137
3
110
134
137
130
3
8
154
Ha-Kabel
8
8
130
Yo
137
134
110
139
Ha-Vorhalle
8
3
134
8
110
Gbf Ost
137
139
Hbf
Hagen
Ha-Heubing
12
134
Gbf
Rehsiepen
137
Ha-Haspe
3
3
139
137
139
12
Gevelsberg West
134
3
22
134
Schwelm-Loh
12/13
3

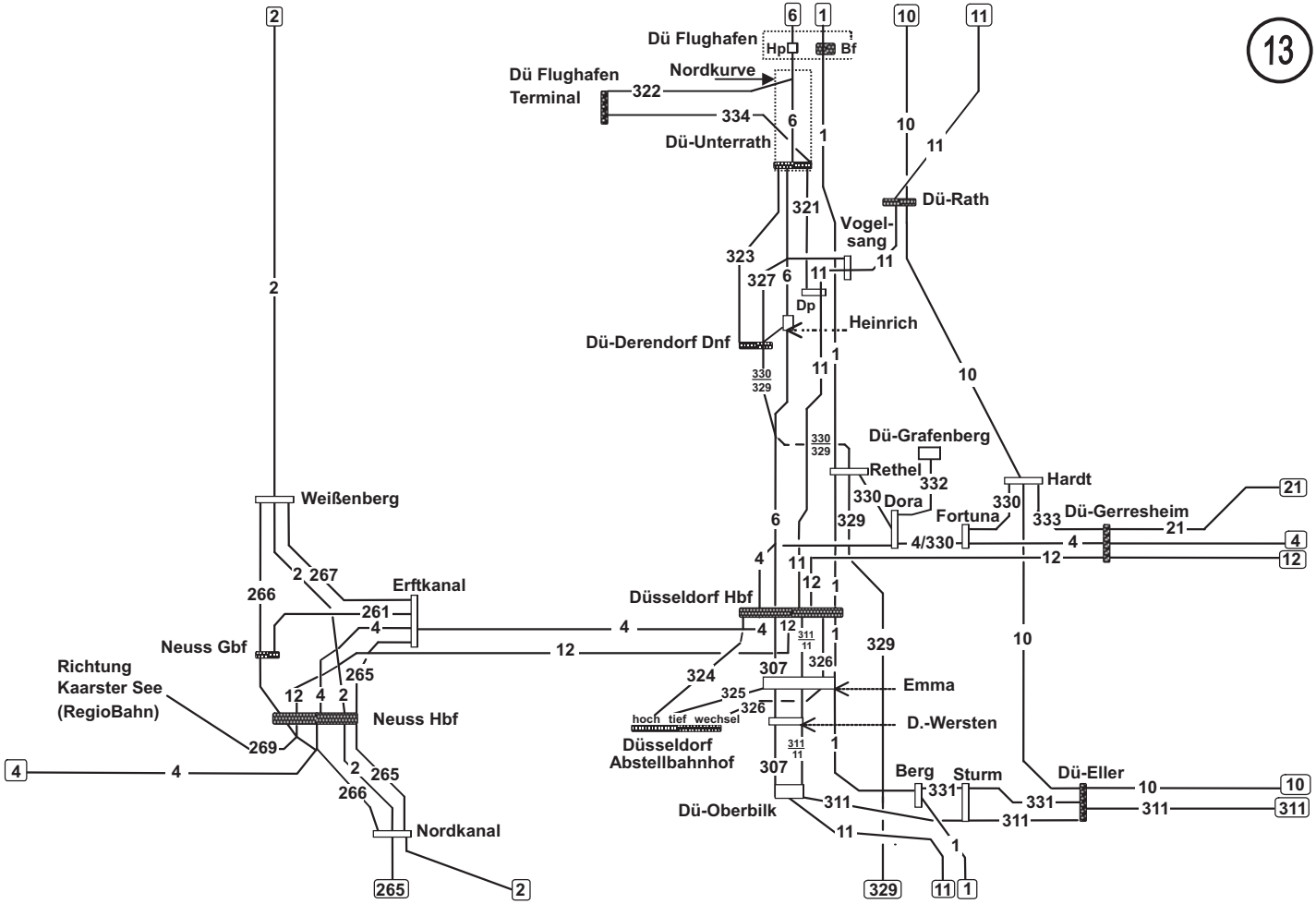
Dü Flughafen
Hp
Bf
Dü Flughafen Terminal
Nordkurve
Dü-Unterrath
Dü-Rath
Vogel-sang
Dp
Heinrich
Dü-Derendorf Dnf
Dü-Grafenberg
Rethel
Hardt
Dora
Fortuna
Dü-Gerresheim
Weißenberg
Erftkanal
Düsseldorf Hbf
Neuss Gbf
Richtung Kaarster See (RegioBahn)
Neuss Hbf
Emma
D.-Wersten
hoch tief wechsel
Düsseldorf Abstellbahnhof
Berg
Sturm
Dü-Eller
Dü-Oberbilk
Nordkanal

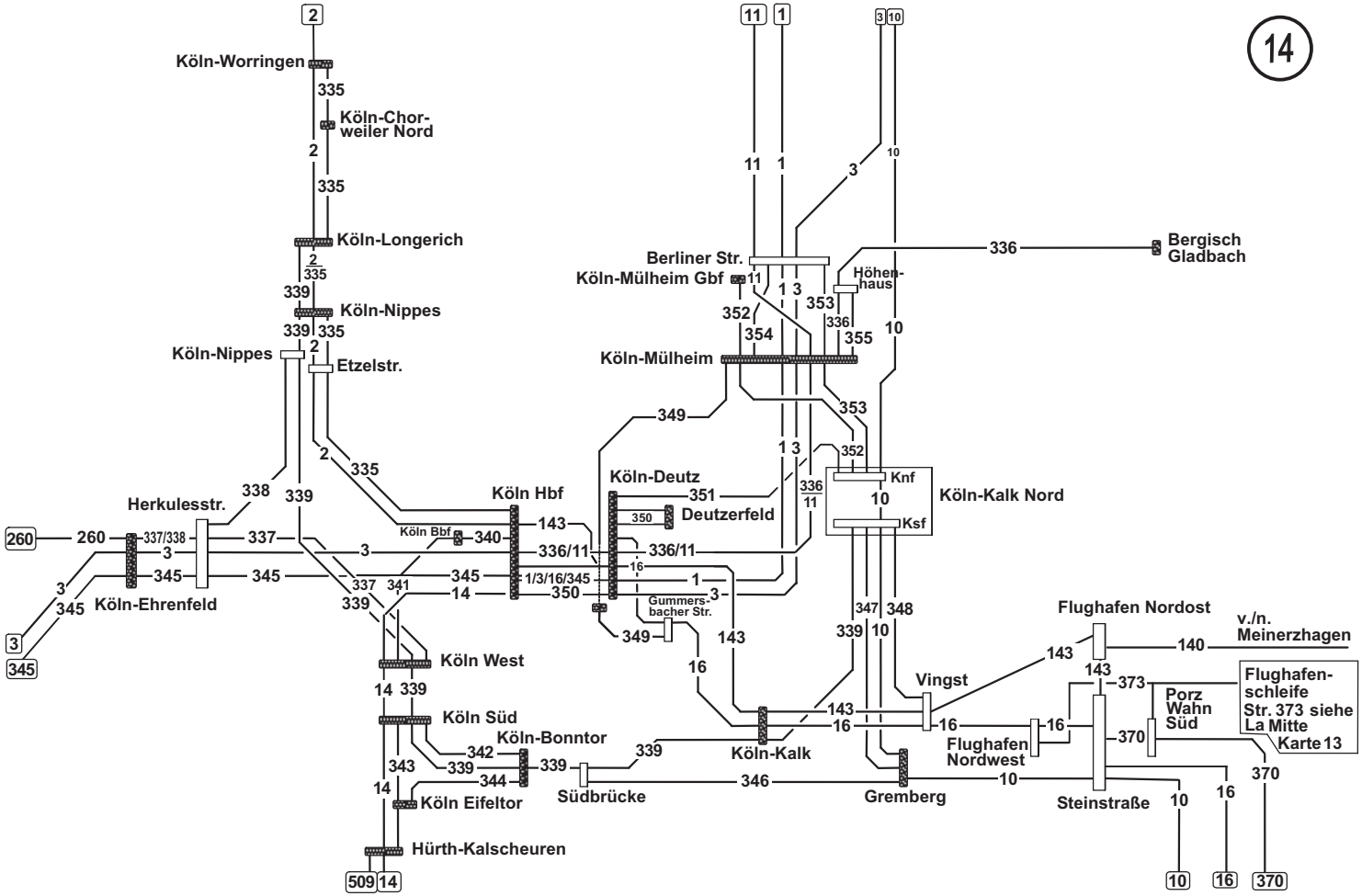
14
Köln-Worringen
Köln-Chor-
weiler Nord
Köln-Longerich
Köln-Nippes
Köln-Nippes
Etzelstr.
Herkulesstr.
Köln-Ehrenfeld
Köln Hbf
Köln Bbf
Köln West
Köln Süd
Köln-Bonntor
Köln Eifeltor
Hürth-Kalscheuren
Köln-Deutz
Deutzerfeld
Gummers-
bacher Str.
Berliner Str.
Köln-Mülheim Gbf
Höhen-
haus
Köln-Mülheim
Bergisch
Gladbach
Knf
Ksf
Köln-Kalk Nord
Köln-Kalk
Südbrücke
Gremberg
Vingst
Flughafen
Nordwest
Steinstraße
Flughafen Nordost
v./n.
Meinerzhagen
Porz
Wahn
Süd
Flughafen-
schleife
Str. 373 siehe
La Mitte
Karte 13

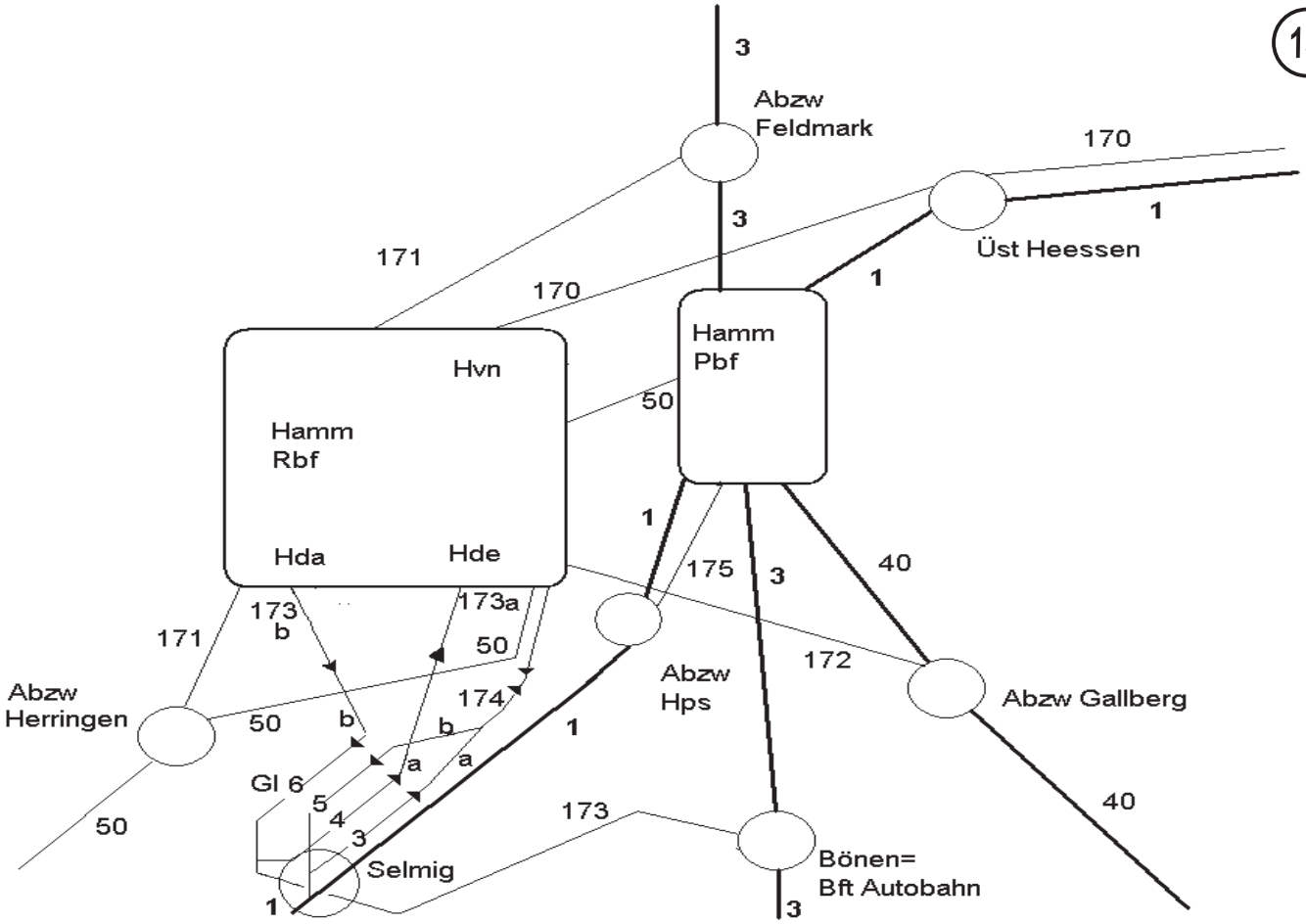
3
Abzw
Feldmark
170
3
1
Üst Heessen
171
170
1
Hamm
Pbf
Hvn
50
Hamm
Rbf
1
Hda
Hde
175
3
40
173
b
173a
171
50
172
Abzw
Hps
Abzw Gallberg
Abzw
Herringen
174
50
b
b
1
a
a
Gl 6
5
4
3
173
40
50
Selmig
Bönen=
Bft Autobahn
1
3

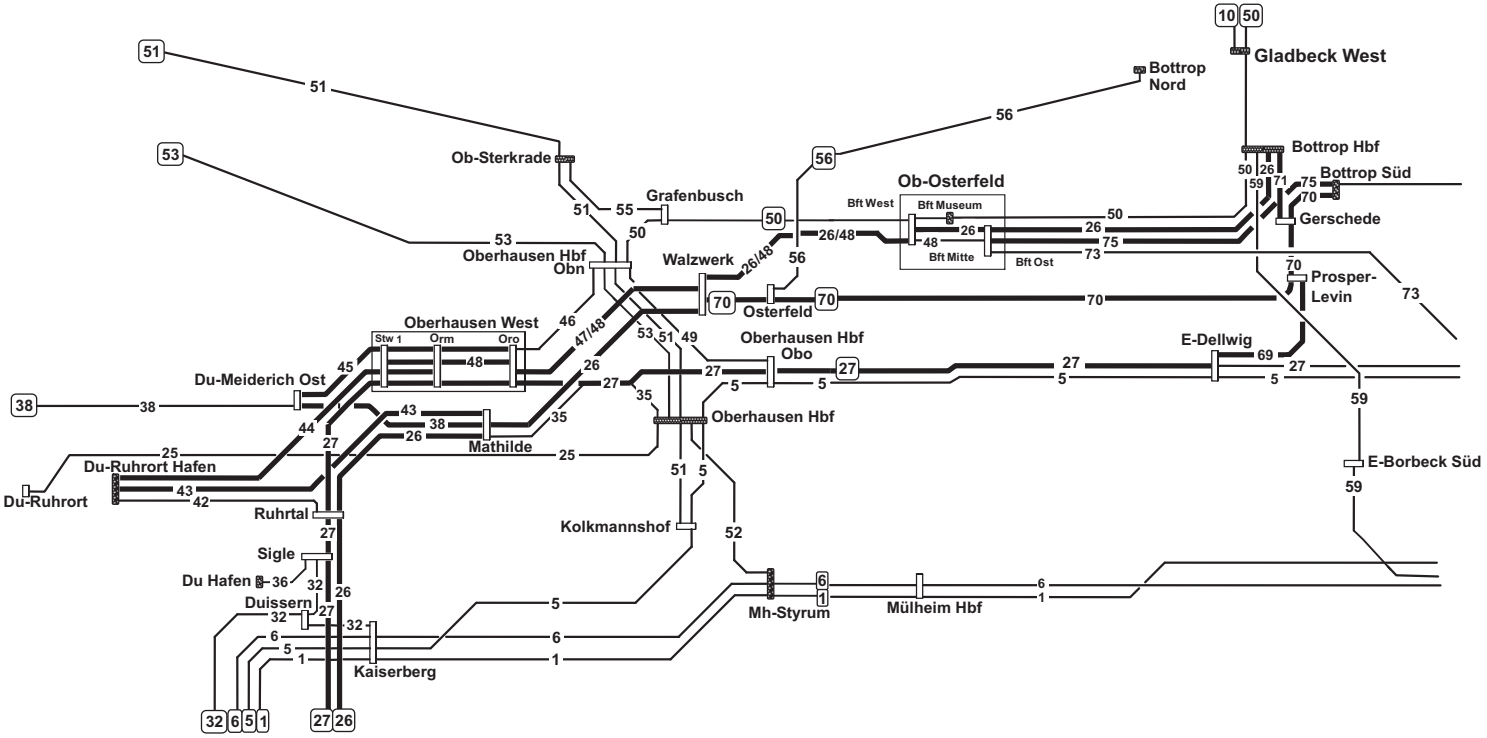
Gladbeck West
Bottrop Nord
Bottrop Hbf
Bottrop Süd
Gerschede
Prosper-Levin
Ob-Sterkrade
Grafenbusch
Ob-Osterfeld
Bft West
Bft Museum
Bft Mitte
Bft Ost
Oberhausen Hbf Obn
Walzwerk
Osterfeld
Oberhausen West
Stw 1
Orm
Oro
Oberhausen Hbf Obo
Oberhausen Hbf
E-Dellwig
E-Borbeck Süd
Du-Meiderich Ost
Mathilde
Du-Ruhrort Hafen
Du-Ruhrort
Ruhrtal
Sigle
Du Hafen
Duissern
Kaiserberg
Kolkmannshof
Mh-Styrum
Mülheim Hbf

DB InfraGO

Übersichtskarten

zum La-Bereich Ost

Gültig ab: 15.12.2024

Netzkarte **La Ost**

Stand: Dezember 2024

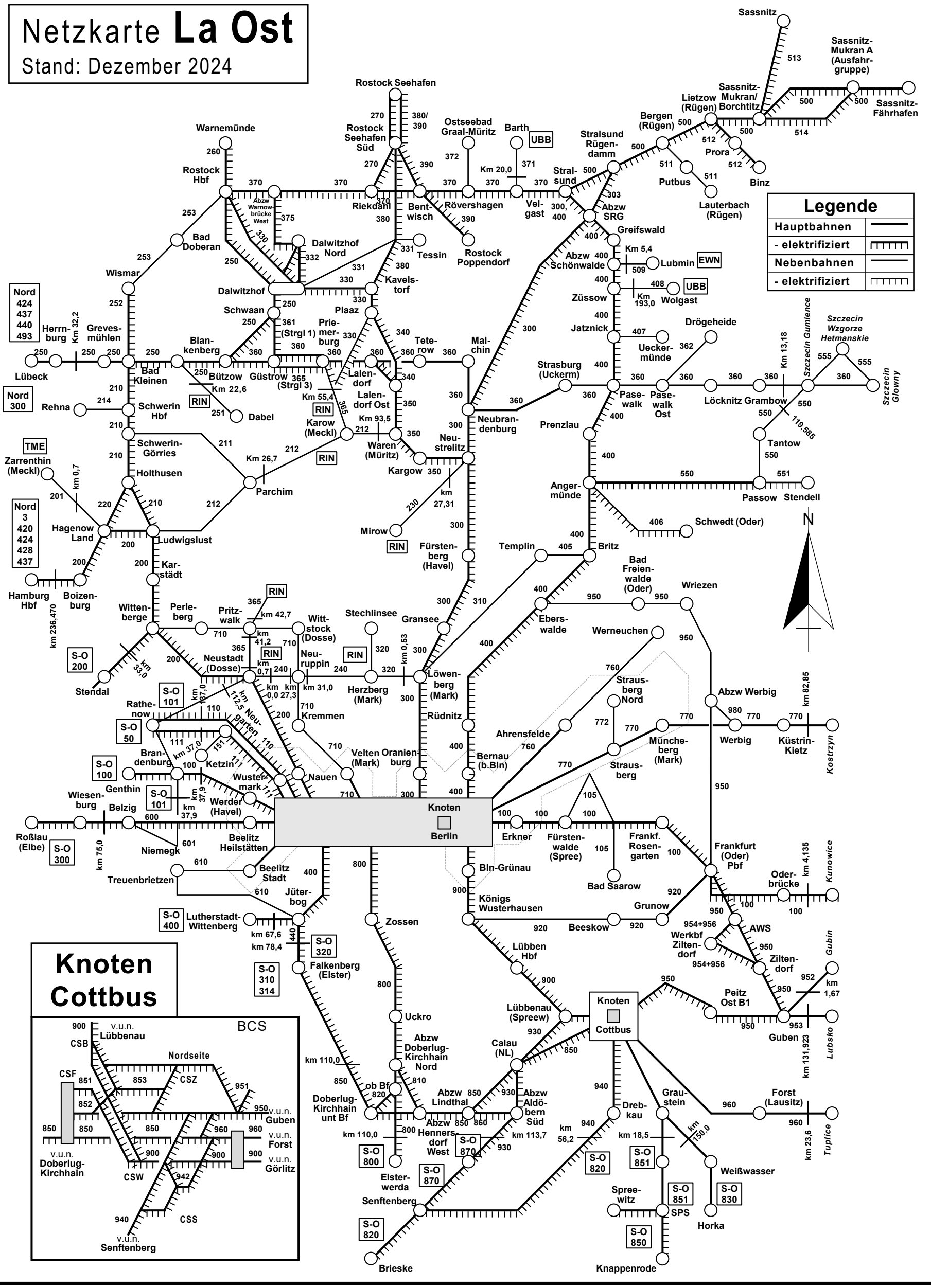

Knoten Berlin

Stand: Juni 2024

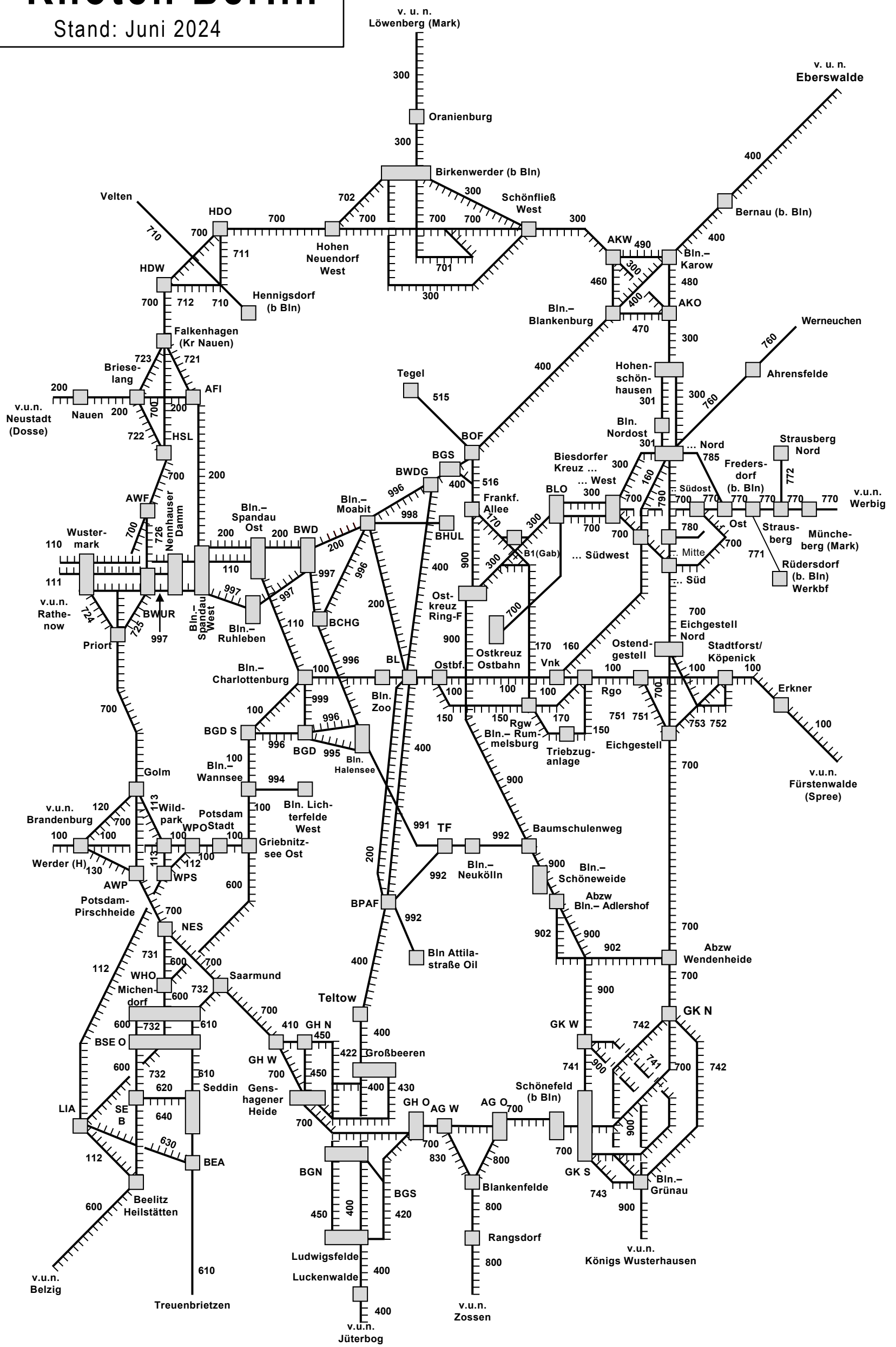

Bereich Berlin Flughafen-Schönefeld – Berlin-Grünau – Königs Wusterhausen La-Strecken

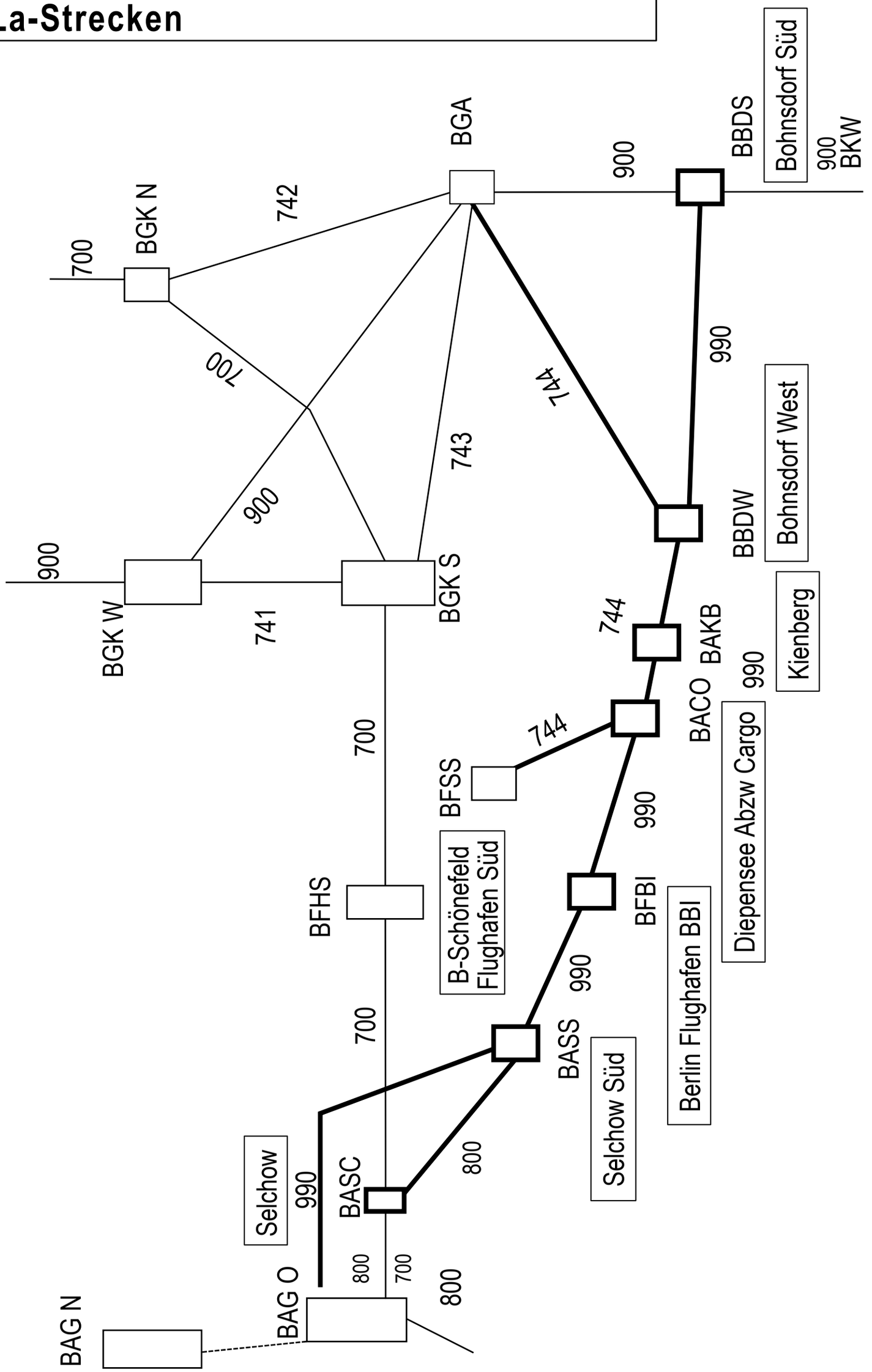

Stand: Juni 2024

DB InfraGO

Übersichtskarten

zum La-Bereich Süd

Gültig ab: 15.12.2024

Streckenkarte La Süd
Teil West

Karte A

Stand: April 2022

Nr. der Anschlußstrecke
La-Bereich Mitte

Aschaffenburg Hbf
Aschaffenburg Süd
Aschaffenburg Hafen
Würzburg Rbf
Würzburg Rbf Zell
Karte 4
Würzburg Hbf
Wertheim
Miltenberg
Lauda
Königshofen (Baden)
M-Friedrichsfeld
Mannheim Hbf
Karte 7
Heidelberg
Eberbach
Seckach
Osterburken
Schwetzingen
Neckargemünd
Mosbach-Neckarelz
Meckesheim
Aglaster-hausen
Germersheim
Graben-Neudorf
Steinsfurt
Bad Friedrichshall Hbf
Eppingen
Heilbronn
Karte 10
Schwäbisch Hall-Hessental
Crailsheim
Ri Nürnberg Hbf
Wörth
Bruchsal
Bretten
Karlsruhe Hbf
Karte 8
K-Durlach
Grötzingen
Mühlacker
Bietigheim-Bissingen
Rastatt
Rastatt-Süd
Pforzheim
Wildbad
Stuttgart Hbf
Karte 2
Aalen
Goldshöfe
Appenweier
Appenw. Kurve
Kehl Grenze
Kehl
Muhrhaag
Bad Griesbach
Weil der Stadt
Hochdorf (b. Horb)
Böblingen
Plochingen
Abzw Windschläg
Freudenstadt Hbf
Eutingen
Wendlingen
Tübingen
Ri Donauwörth
Ülp Offenburg Nord
Offenburg Gbf
Offenburg
Horb
Oberlenningen
6NBS
Ulm Karte 11
Neu Ulm
Günzburg
Neuoffingen
47
Villingen (Schwarzw)
Freiburg (Brsg) Gbf
Neue Messe/Uni
Denzlingen
Elzach
Hausach
Abzw Gundelfingen
Rottweil
Inzigkofen
Mengen
Laupheim West
Laupheim Stadt
Breisach
Freiburg Hbf
Abzw Leutersberg
Titisee
Seebrugg
Tuttlingen
Herbertingen
Aulendorf
Memmingen
Neuenburg (Baden)
Müllheim (Baden)
Schliengen Nord
Hattingen (Baden)
Donaueschingen
Immendingen
Stahringen
Zell (Wiesental)
Haltingen
Weil(Rhein)
Lörrach
Radolfzell
Kißlegg
Hergatz
Basel Bad Bf
Karte 9
Waldshut
Singen (Hohentw)
Konstanz
Koblenz SBB
Friedrichshafen Hafen
Stadt
Lindau Hbf
Lindau -Reutin
Grenze
Basel SBB PB
Basel SBB Rb

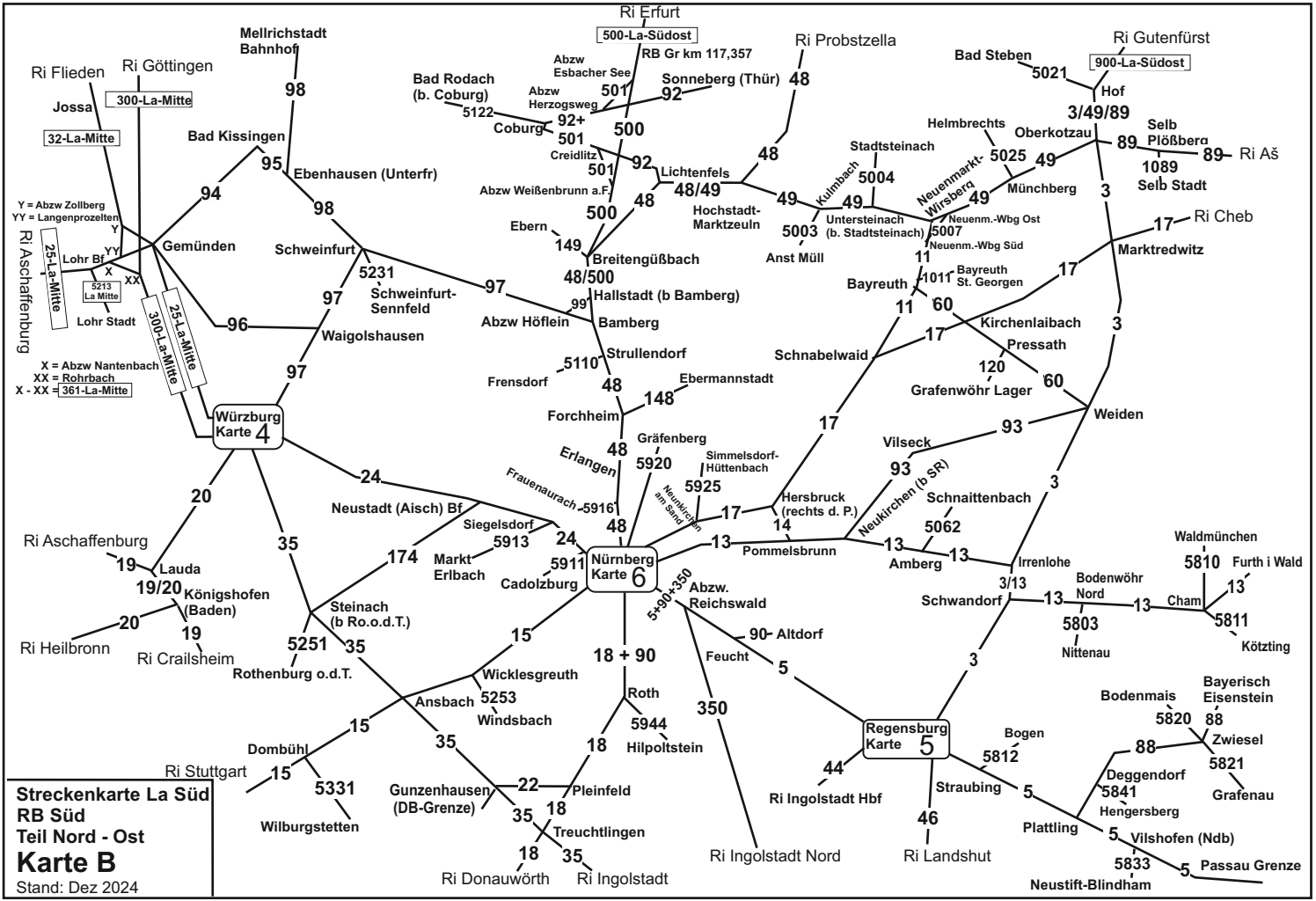
Ri Erfurt
500-La-Südost
RB Gr km 117,357
Ri Probstzella
Ri Gutenfürst
900-La-Südost
Bad Steben
5021
Hof
3/49/89
Selb Plößberg
89
Ri Aš
1089
Selb Stadt
Oberkotzau
Helmbrechts
5025
49
Münchberg
Neuenmarkt-Wirsberg
Stadtsteinach
5004
Kulmbach
Untersteinach (b. Stadtsteinach)
5007
Neuenm.-Wbg Ost
Neuenm.-Wbg Süd
Anst Müll
5003
Hochstadt-Marktzeuln
Lichtenfels
48/49
Abzw Esbacher See
Abzw Herzogsweg
Sonneberg (Thür)
Bad Rodach (b. Coburg)
5122
Coburg
92+
501
500
Creidlitz
Abzw Weißenbrunn a.F.
Ebern
149
Breitengüßbach
48/500
Hallstadt (b Bamberg)
Abzw Höflein
Bamberg
Strullendorf
5110
Frensdorf
Ebermannstadt
148
Forchheim
Gräfenberg
5920
Simmelsdorf-Hüttenbach
5925
Erlangen
Frauenaurach
5916
Neunkirchen am Sand
Nürnberg Karte 6
Abzw. Reichswald
5+90+350
Altdorf
90
Feucht
350
18 + 90
Roth
5944
Hilpoltstein
Pleinfeld
Treuchtlingen
Ri Ingolstadt
Ri Donauwörth
Gunzenhausen (DB-Grenze)
22
Wicklesgreuth
5253
Windsbach
Ansbach
Steinach (b Ro.o.d.T.)
5251
Rothenburg o.d.T.
Siegelsdorf
5913
Markt Erlbach
5911
Cadolzburg
Neustadt (Aisch) Bf
Ri Aschaffenburg
Lauda
19/20
Königshofen (Baden)
Ri Heilbronn
Ri Crailsheim
Ri Stuttgart
Dombühl
5331
Wilburgstetten
Würzburg Karte 4
Ri Flieden
Ri Göttingen
Jossa
300-La-Mitte
32-La-Mitte
Mellrichstadt Bahnhof
Bad Kissingen
Ebenhausen (Unterfr)
Y = Abzw Zollberg
YY = Langenprozelten
Gemünden
Lohr Bf
25-La-Mitte
5213 La Mitte
Lohr Stadt
X = Abzw Nantenbach
XX = Rohrbach
X - XX = 361-La-Mitte
Ri Aschaffenburg
Schweinfurt
5231
Schweinfurt-Sennfeld
Waigolshausen
Ri Cheb
Marktredwitz
Bayreuth
1011
Bayreuth St. Georgen
Kirchenlaibach
Pressath
120
Grafenwöhr Lager
Schnabelwaid
Weiden
Vilseck
Schnaittenbach
5062
Hersbruck (rechts d. P.)
Pommelsbrunn
Amberg
Irrenlohe
Neukirchen (b SR)
Schwandorf
3/13
Bodenwöhr Nord
5803
Nittenau
Waldmünchen
5810
Furth i Wald
Cham
5811
Kötzting
Regensburg Karte 5
Bogen
5812
Straubing
Ri Ingolstadt Hbf
Ri Ingolstadt Nord
Ri Landshut
Bodenmais
5820
Bayerisch Eisenstein
88
Zwiesel
5821
Grafenau
Deggendorf
5841
Hengersberg
Plattling
Vilshofen (Ndb)
5833
Neustift-Blindham
Passau Grenze
Streckenkarte La Süd
RB Süd
Teil Nord - Ost
Karte B
Stand: Dez 2024

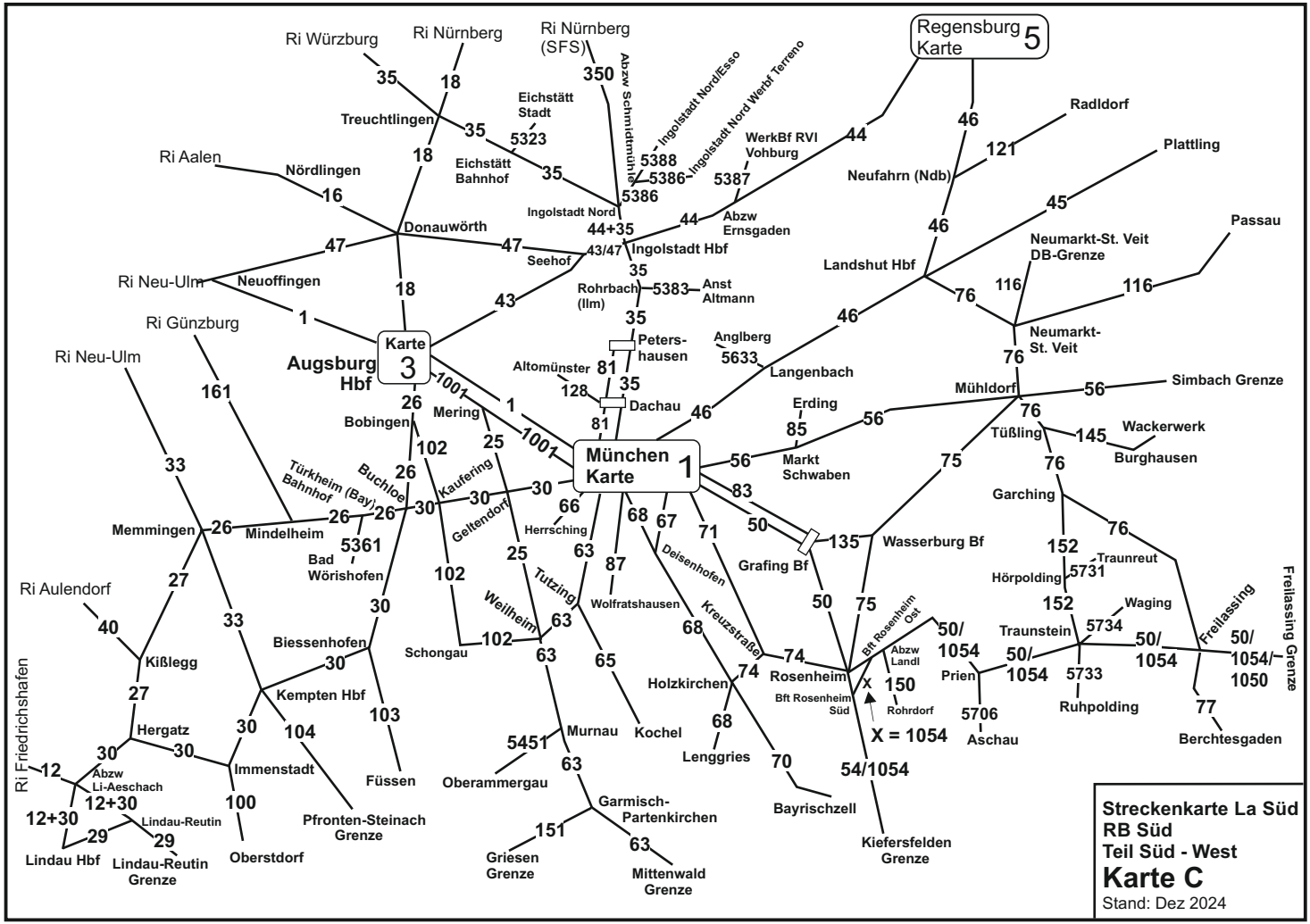

Streckenkarte La Süd
RB Süd
Teil Süd - West
Karte C
Stand: Dez 2024

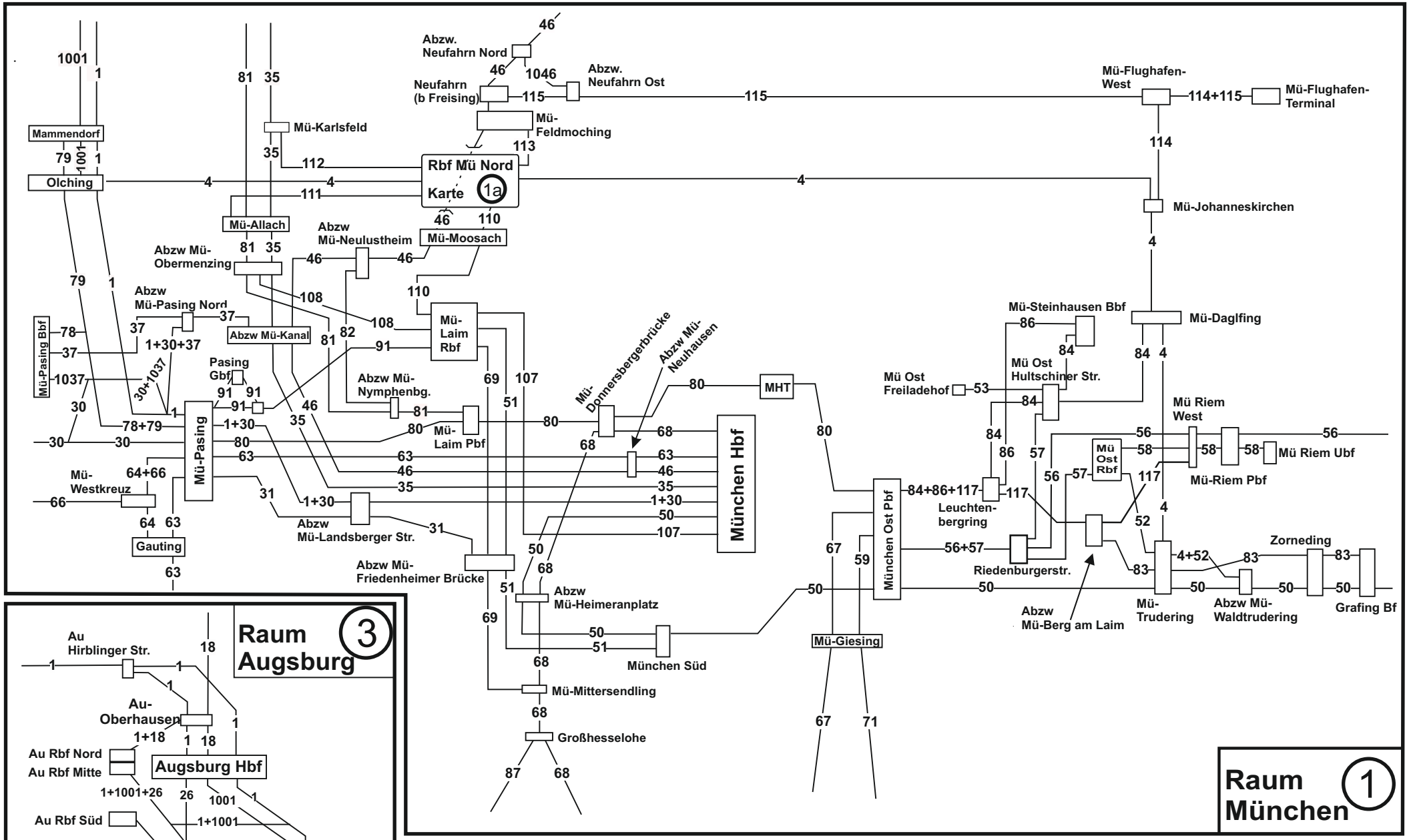

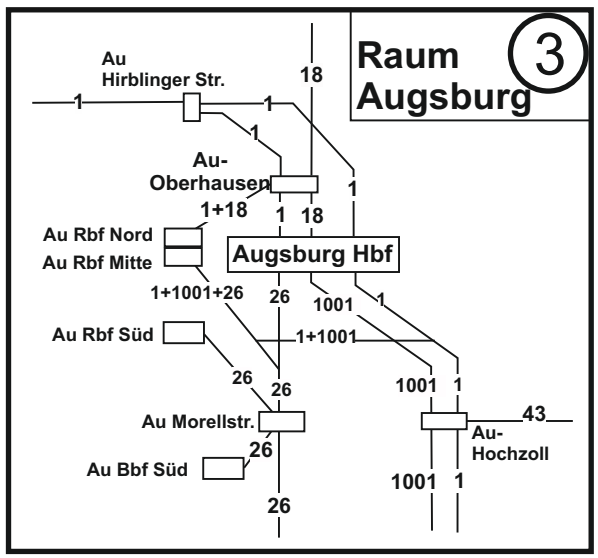

Zeichenerklärung:

MH T = Mü Hbf Tunnelbahnhof

Stand Juli 2018

La - Übersichtskarte und Streckenverknüpfung
Rbf Mü Nord

1a

Stand: Dez 2024

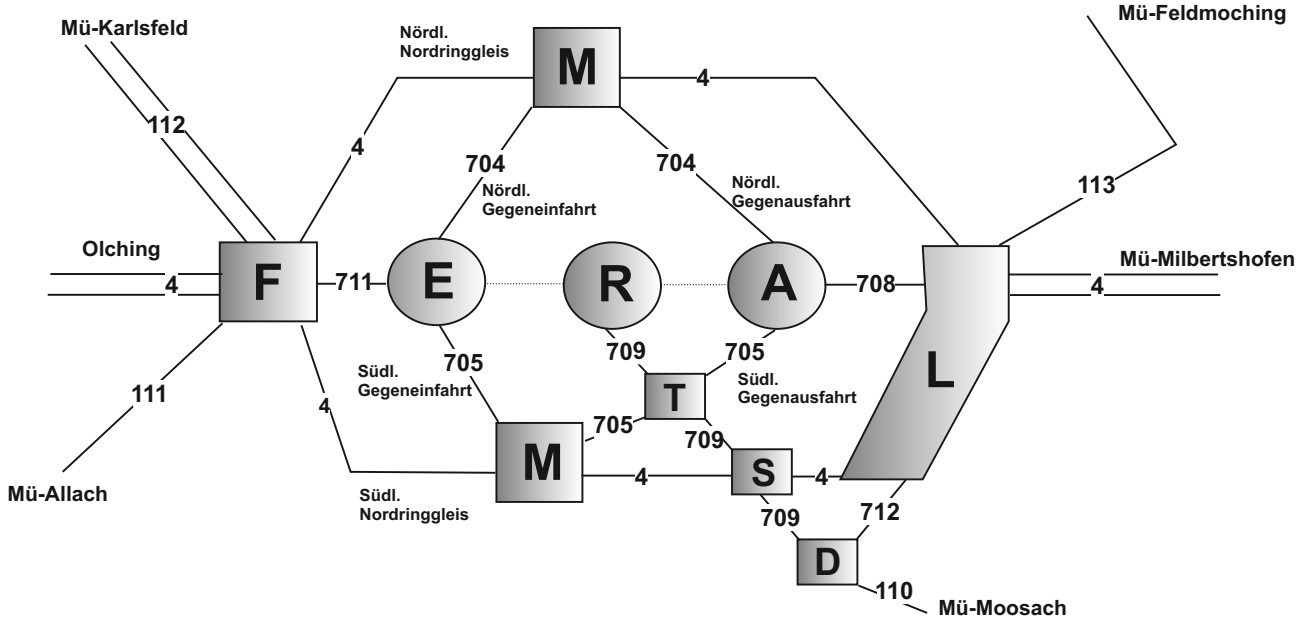

F Mü Nord Forstweg (MN F)

M Bft Mü Nord Mitte (Süd und Nord) (MN M)

L Mü Nord Lasallestraße (MN L)

R Bft Mü Nord Richtungsgruppe Gl 311-318 (MN R)

E Bft Mü Nord Einfahrgruppe (MN E)

A Bft Mü Nord Ausfahrgruppe (MN A)

T Mü Nord Richtungsgruppe Mitte (MN T)

S Mü Nord Richtungsgruppe Süd (MN S)

D Mü Nord Einfahrt Moosach (MN D)

Raum Stuttgart 2

Stand: Dez 2021

Ri Heilbronn
20
Ri Mühlacker
1
Bietigheim-Bissingen
1 1
28
Ri Backnang
Ludwigsburg
Ri Vaihingen (E)
310
811/1
1 1
Abzw Karlshöhe
7
Kornwestheim Rbf
1 1
Kornwestheim Pbf
310
811/1
7
1 1
7
Stg Zuffenhausen
Bft Zazenhausen
73
310
Renningen
73
73
Korntal
73
Weil der Stadt
1/310
Stg-Zuffenhausen Bft
Abzw Pragtunnel
7
Abzw Nürnberger Straße
Ri Backnang
61
1
Stuttgart Nord
1/310
Fellbach
15
15
Ri Aalen
34
1
Stg-Bad Cannstatt
15
15
15
15
Waiblingen
Stg Hbf Einmündung Nord
34
1 / 15
15
1
1/15
7
15
73
Stuttgart Hbf
806
1
1
34
Tunnel
Bft Stg-Utürkhm 526 f
806
Stg - Untertürkheim Gbf
8
Schwabstraße mit Bft Wendeanlage
7
807
Neckarpark
8
Stg - Untertürkheim Pbf
890
813
Stg Ost
Stg Hafen
1 1
34
Stg-Vaihingen mit Bft Stg Rohr
Esslingen (Neckar)
1 1
34
8
Filderstadt
Plochingen
Wendlingen
Böblingen
32
6 NBS
1
Ri Horb
Ri Tübingen
Ri Ulm

Raum Heilbronn 10

Ri Bad Friedrichshall
20
Ri Schwäbisch Hall
62
Bft Heilbronn Pbf
Ri Eppingen
62
20
Bft Gbf
Sig R 140
20 20
Bft Klingenberg
Sig R 240
20
Heilbronn Sig A
20
Ri Bietigheim

Raum Ulm 11

Ri Plochingen
Wendlingen 6 NBS
Ulm Hbf Einm. Nord
1
1
10
Ri Aalen
Ulm Söflingen
39
39
39
10
Ri Günzburg
Ri Herbertingen
Ulm Rbf
1
Ulm Hbf
1
1
10
Neu Ulm
33
10
Ri Memmingen
Ri Aulendorf

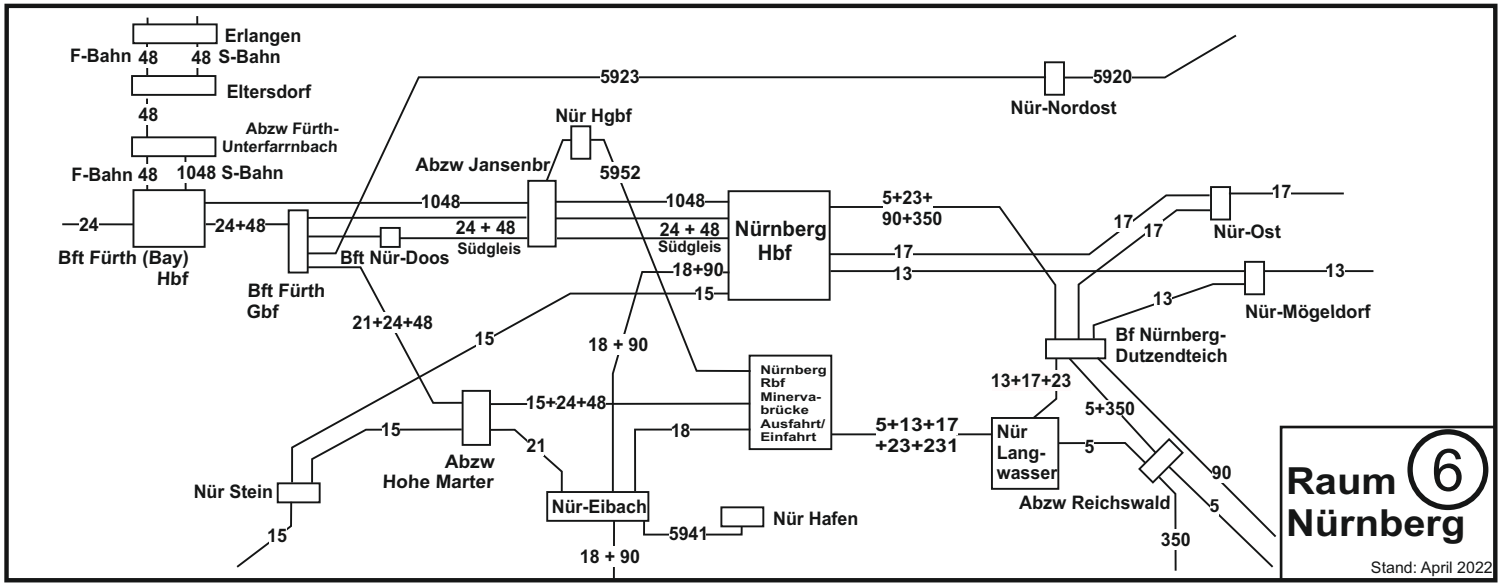
Erlangen
F-Bahn 48
48 S-Bahn
Eltersdorf
48
Abzw Fürth-Unterfarrnbach
F-Bahn 48
1048 S-Bahn
24
24+48
Bft Fürth (Bay) Hbf
Bft Fürth Gbf
Bft Nür-Doos
1048
24 + 48
Südgleis
Abzw Jansenbr
Nür Hgbf
5952
5923
5920
Nür-Nordost
1048
24 + 48
Südgleis
Nürnberg Hbf
5+23+ 90+350
17
13
18+90
15
17
17
Nür-Ost
13
Nür-Mögeldorf
13
Bf Nürnberg-Dutzendteich
21+24+48
15
18 + 90
Nürnberg Rbf Minerva-brücke Ausfahrt/ Einfahrt
15+24+48
15
21
18
Abzw Hohe Marter
Nür Stein
15
Nür-Eibach
5941
Nür Hafen
18 + 90
5+13+17 +23+231
Nür Lang-wasser
13+17+23
5+350
5
90
5
350
Abzw Reichswald
Raum Nürnberg 6
Stand: April 2022

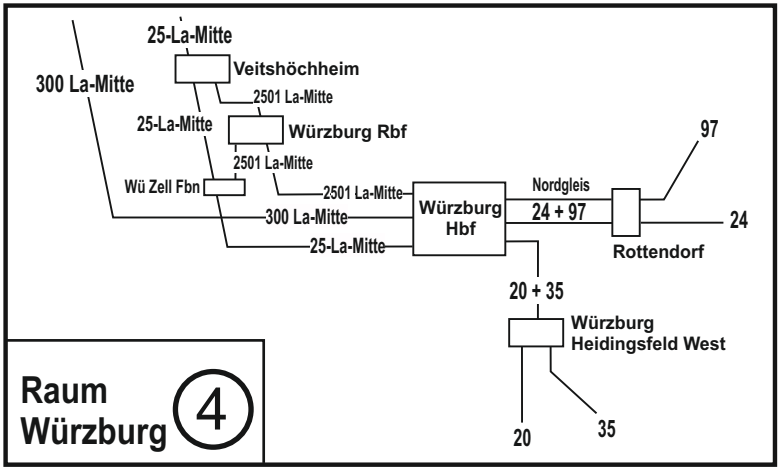
25-La-Mitte
Veitshöchheim
300 La-Mitte
2501 La-Mitte
25-La-Mitte
Würzburg Rbf
2501 La-Mitte
Wü Zell Fbn
2501 La-Mitte
300 La-Mitte
25-La-Mitte
Würzburg Hbf
Nordgleis
24 + 97
97
24
Rottendorf
20 + 35
Würzburg Heidingsfeld West
20
35
Raum Würzburg 4

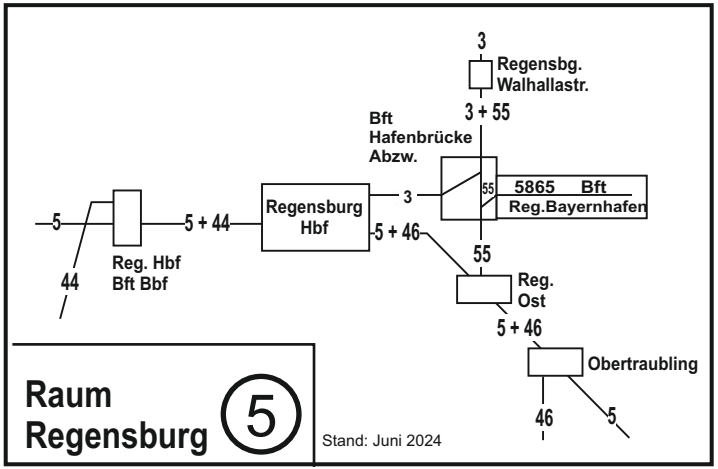
3
Regensbg. Walhallastr.
3 + 55
Bft Hafenbrücke Abzw.
3
55
5865 Bft Reg.Bayernhafen
5
5 + 44
Regensburg Hbf
5 + 46
44
Reg. Hbf Bft Bbf
55
Reg. Ost
5 + 46
Obertraubling
46
5
Raum Regensburg 5
Stand: Juni 2024

Stand: Dez 2024

Raum Mannheim - Heidelberg

7

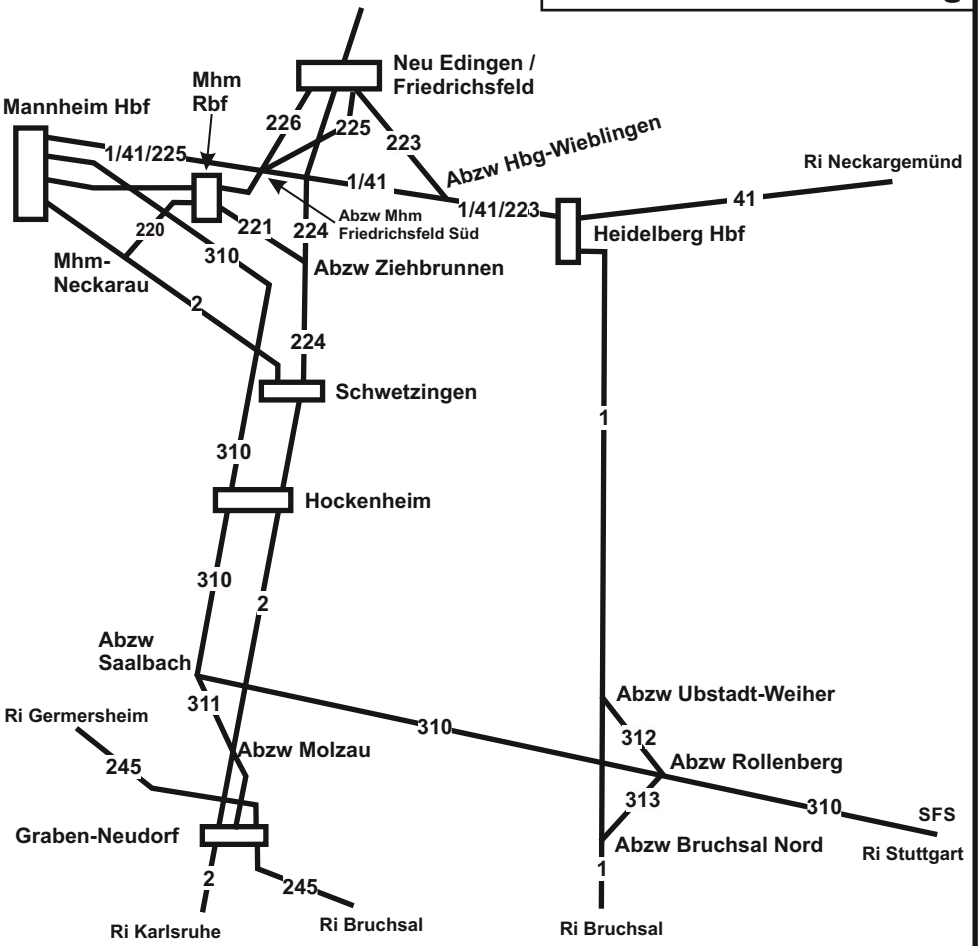

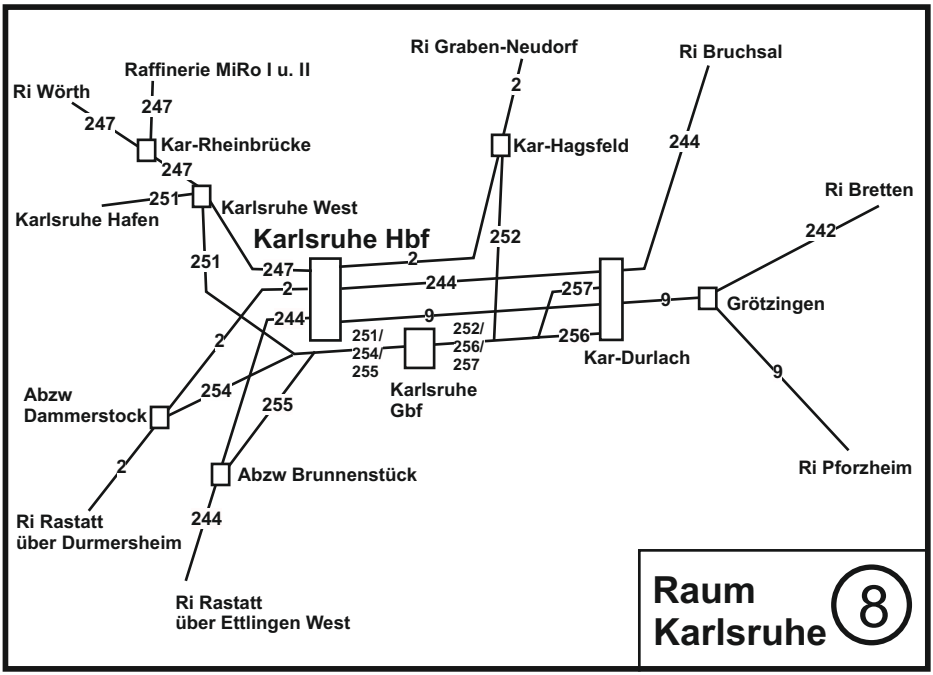
Raum Karlsruhe
8
Ri Wörth
Raffinerie MiRo I u. II
247
247
Kar-Rheinbrücke
247
251
Karlsruhe Hafen
Karlsruhe West
Karlsruhe Hbf
251
247
2
2
244
244
9
2
Ri Graben-Neudorf
2
Kar-Hagsfeld
252
Ri Bruchsal
244
257
256
Kar-Durlach
9
Grötzingen
Ri Bretten
242
9
Ri Pforzheim
251/
254/
255
252/
256/
257
Karlsruhe
Gbf
Abzw
Dammerstock
254
255
2
Abzw Brunnenstück
Ri Rastatt
über Durmersheim
244
Ri Rastatt
über Ettlingen West

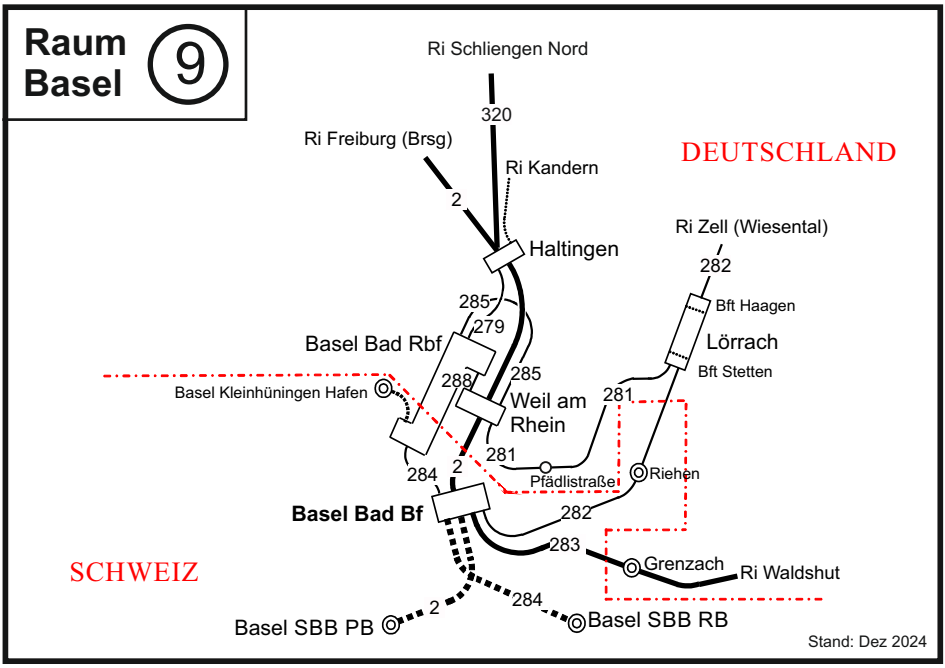
Raum Basel
9
Ri Schliengen Nord
320
Ri Freiburg (Brsg)
Ri Kandern
2
DEUTSCHLAND
Haltingen
Ri Zell (Wiesental)
282
Bft Haagen
Lörrach
Bft Stetten
285
279
Basel Bad Rbf
Basel Kleinhüningen Hafen
288
285
Weil am
Rhein
281
281
284
2
Pfädlistraße
Riehen
Basel Bad Bf
282
283
Grenzach
Ri Waldshut
SCHWEIZ
284
2
Basel SBB PB
Basel SBB RB
Stand: Dez 2024

Übersichtskarten

zum La-Bereich Südost

Gültig ab: 15.12.2024

Netzkarte La-Südost

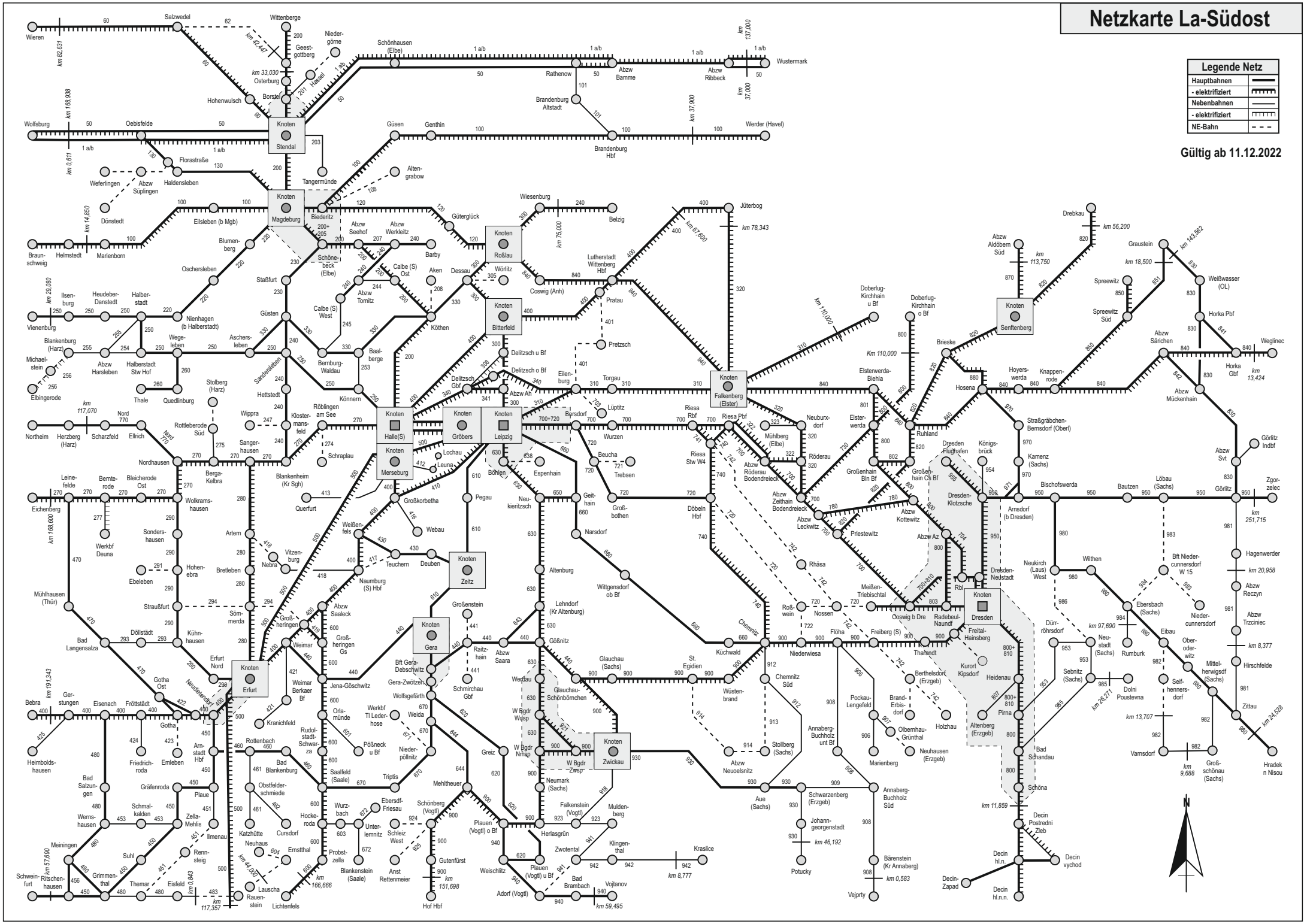

Leipzig

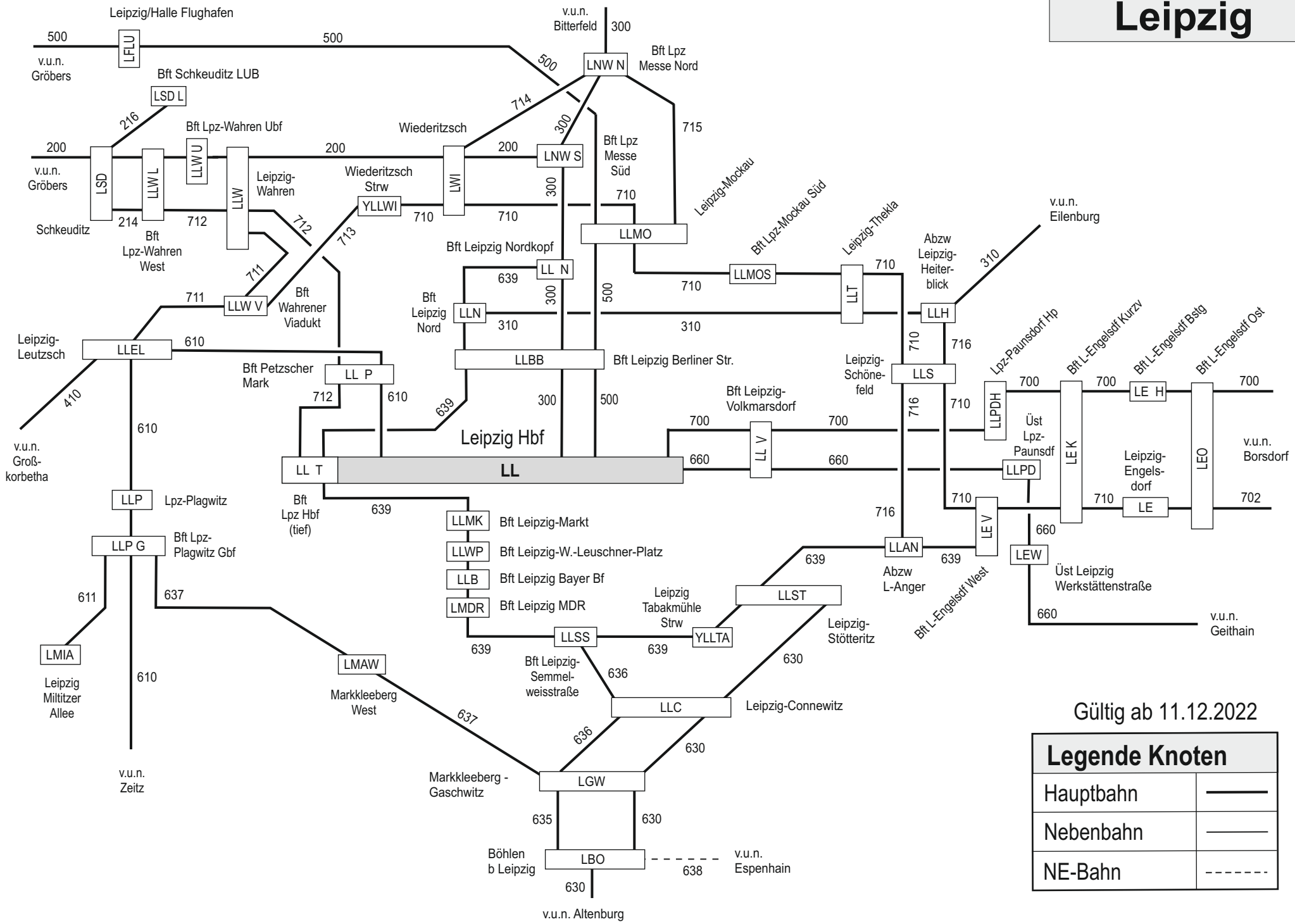

Gültig ab 11.12.2022

Legende Knoten	
Hauptbahn	———
Nebenbahn	———
NE-Bahn	- - - - - -

Halle (Saale)

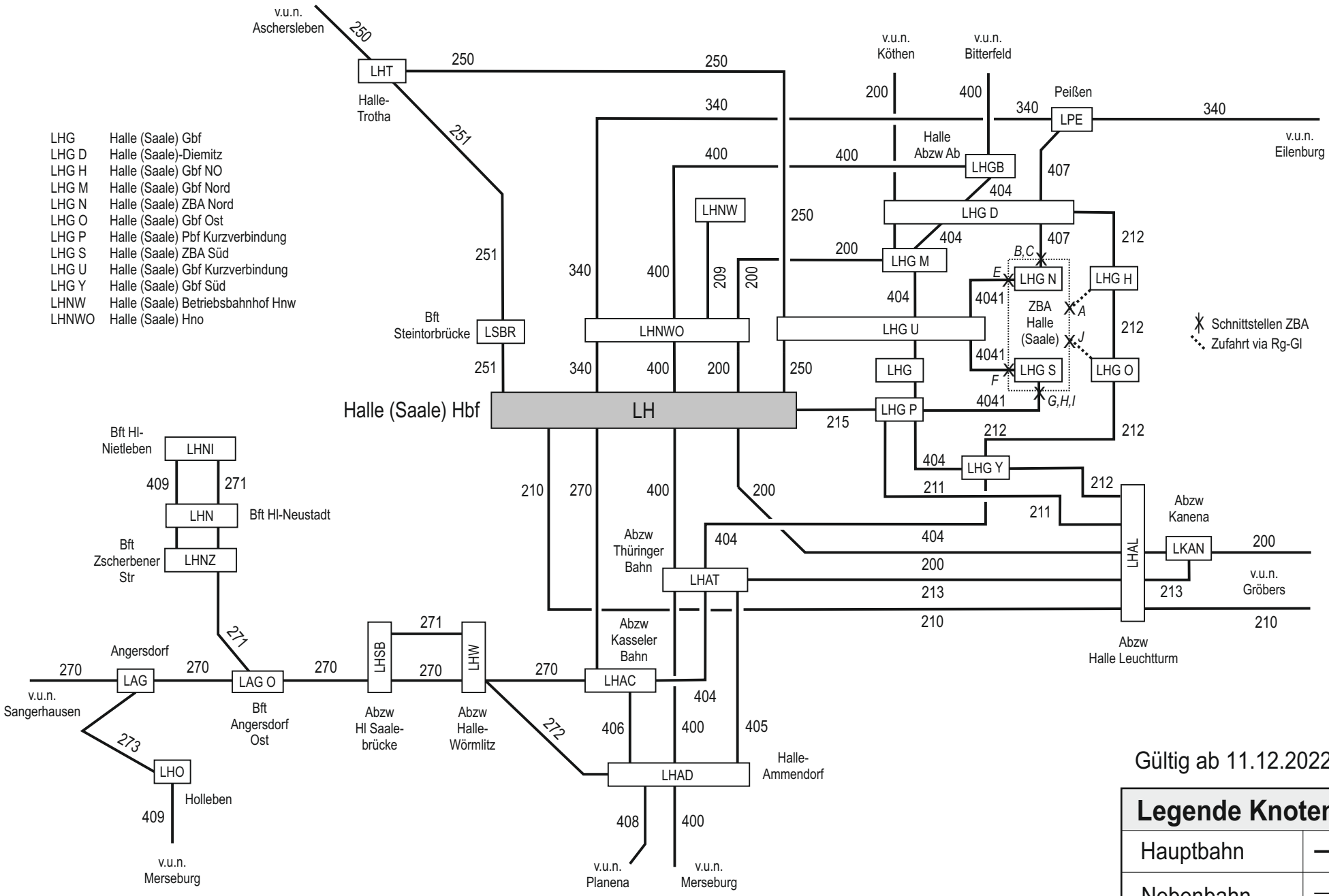

LHG	Halle (Saale) Gbf
LHG D	Halle (Saale)-Diemitz
LHG H	Halle (Saale) Gbf NO
LHG M	Halle (Saale) Gbf Nord
LHG N	Halle (Saale) ZBA Nord
LHG O	Halle (Saale) Gbf Ost
LHG P	Halle (Saale) Pbf Kurzverbindung
LHG S	Halle (Saale) ZBA Süd
LHG U	Halle (Saale) Gbf Kurzverbindung
LHG Y	Halle (Saale) Gbf Süd
LHNW	Halle (Saale) Betriebsbahnhof Hnw
LHNWO	Halle (Saale) Hno

Gültig ab 11.12.2022

Legende Knoten

Hauptbahn	———
Nebenbahn	———

Dresden

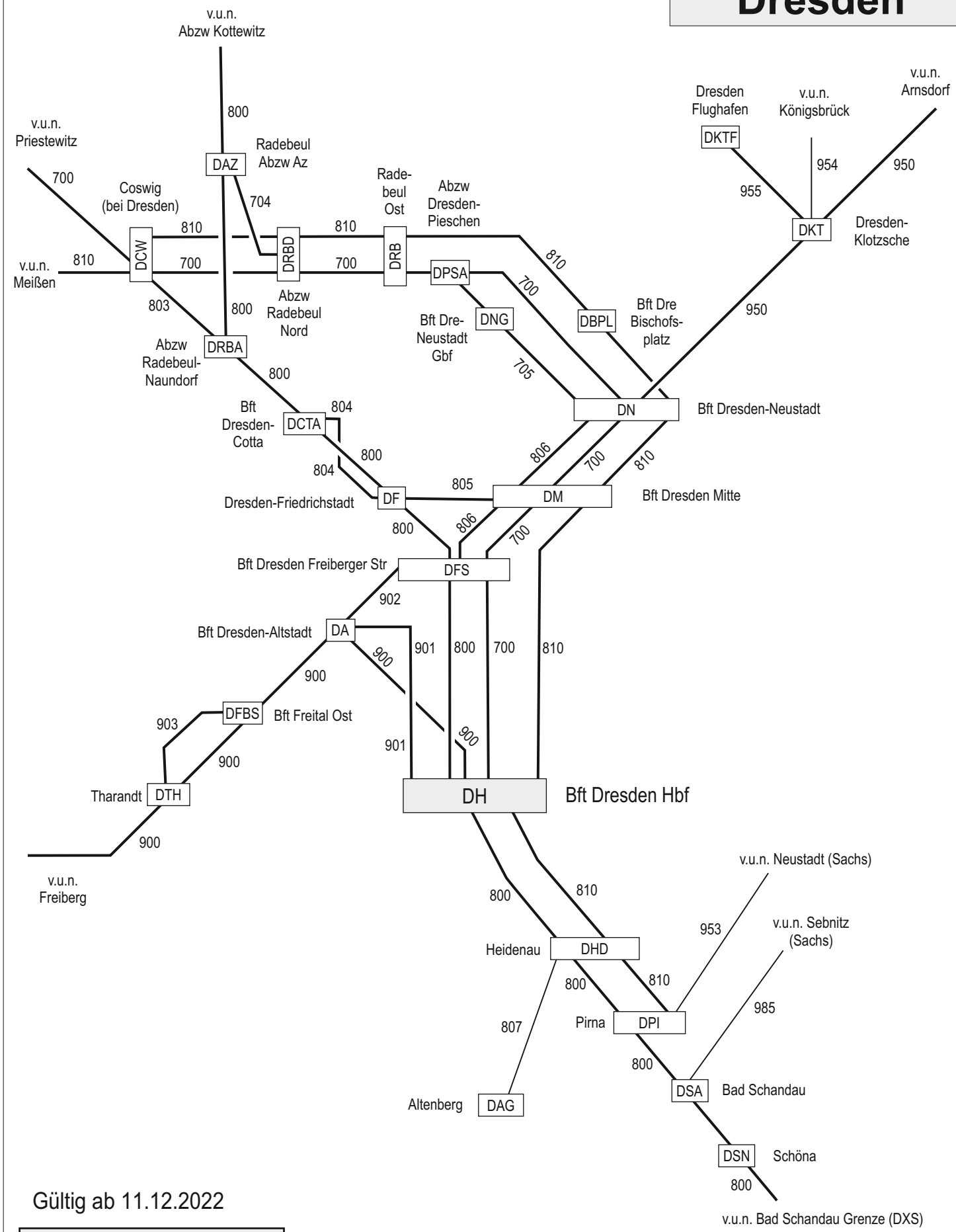

Gültig ab 11.12.2022

Legende Knoten	
Hauptbahn	———
Nebenbahn	———

Merseburg

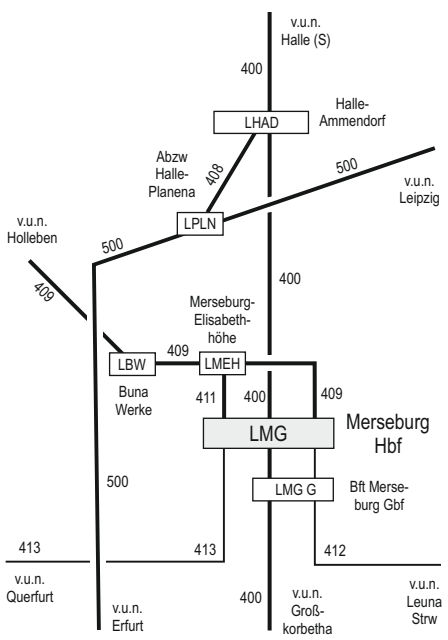

Gröbers

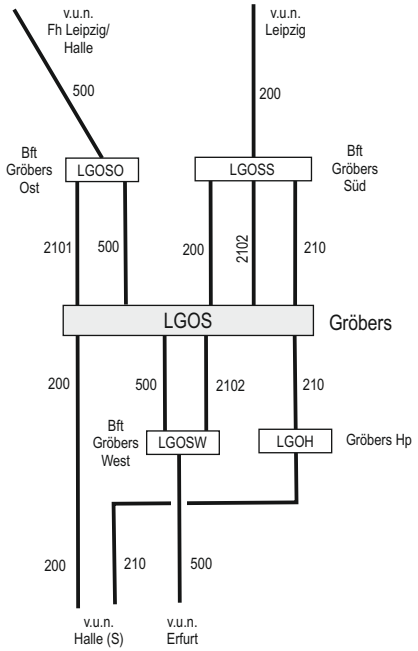

Zeitz

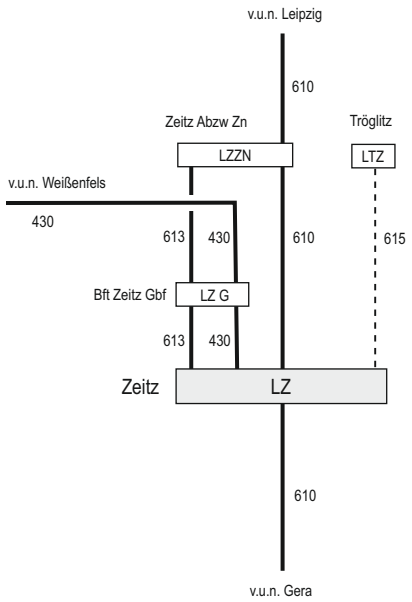

Falkenberg

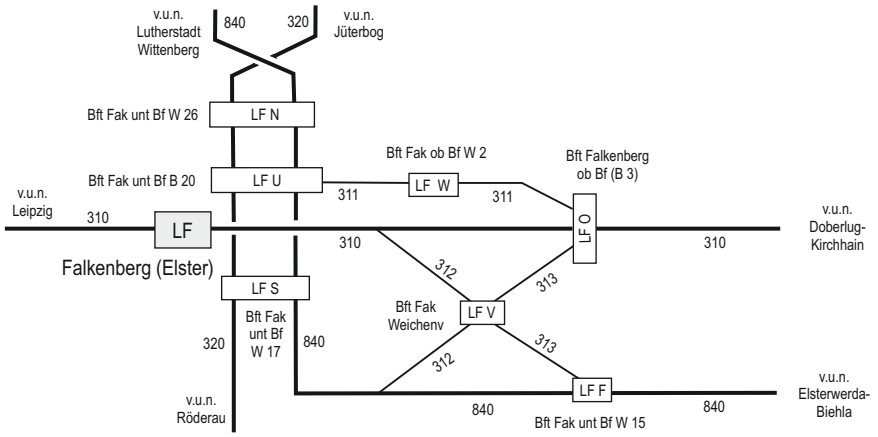

Gera

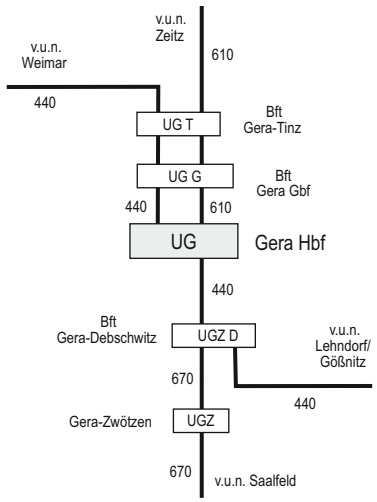

Zwickau

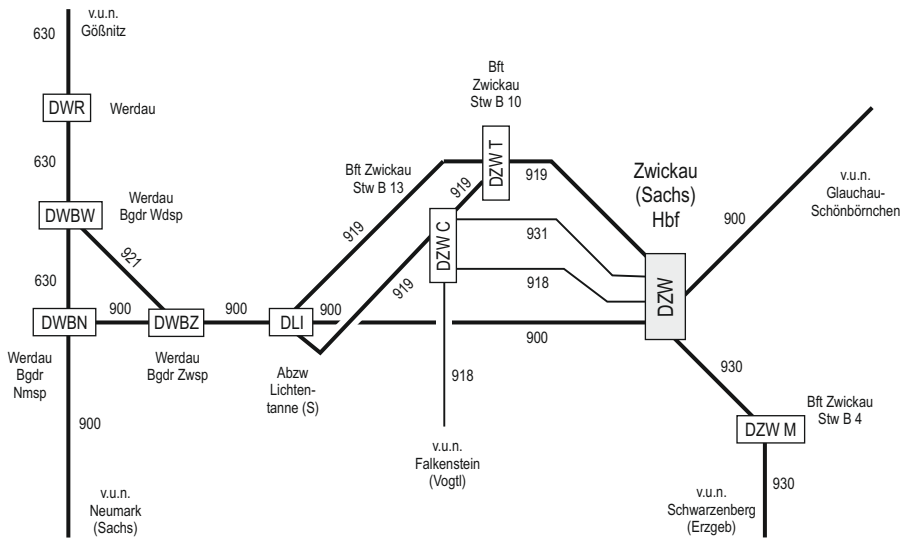

Senftenberg

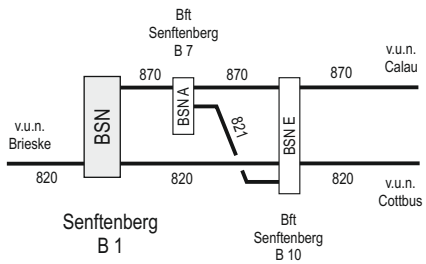

Gültig ab 11.12.2022

Legende Knoten	
Hauptbahn	———
Nebenbahn	———
NE-Bahn	- - - - -

Magdeburg

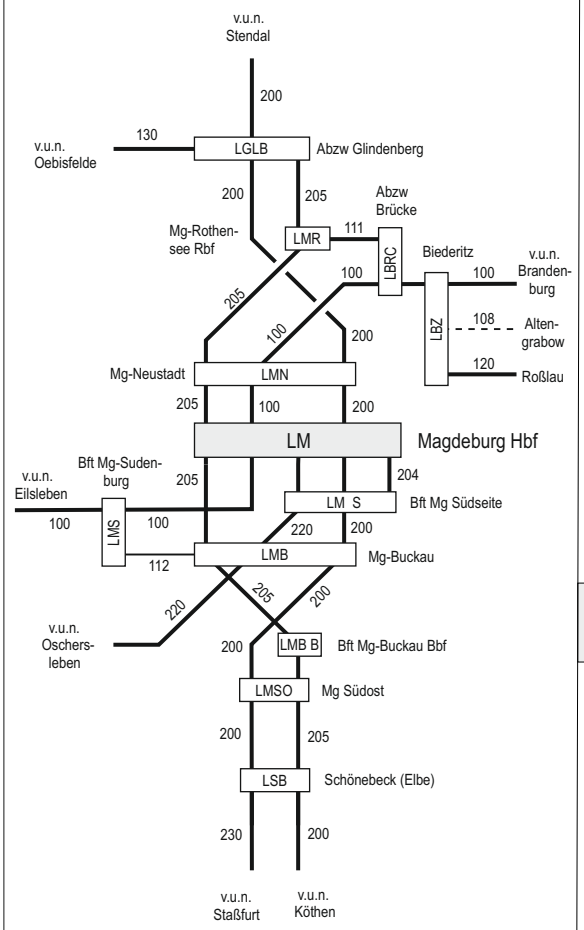

Stendal

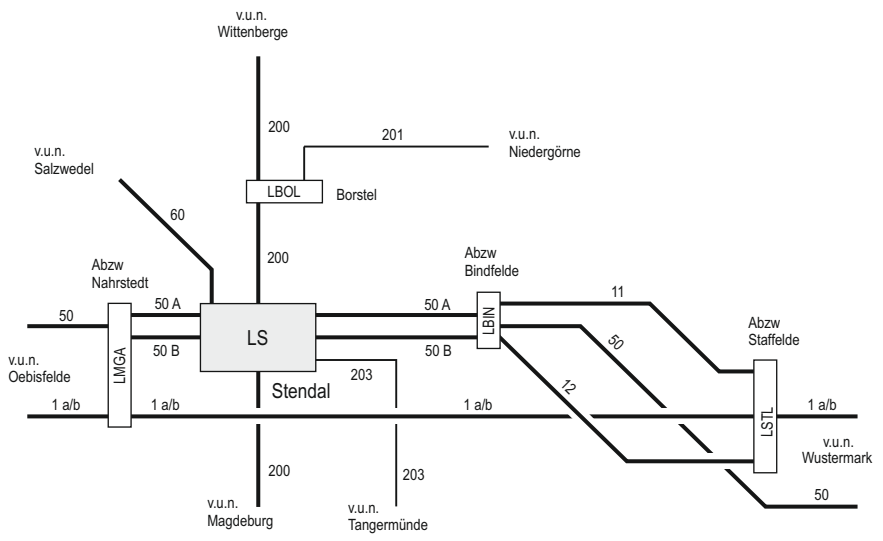

Erfurt

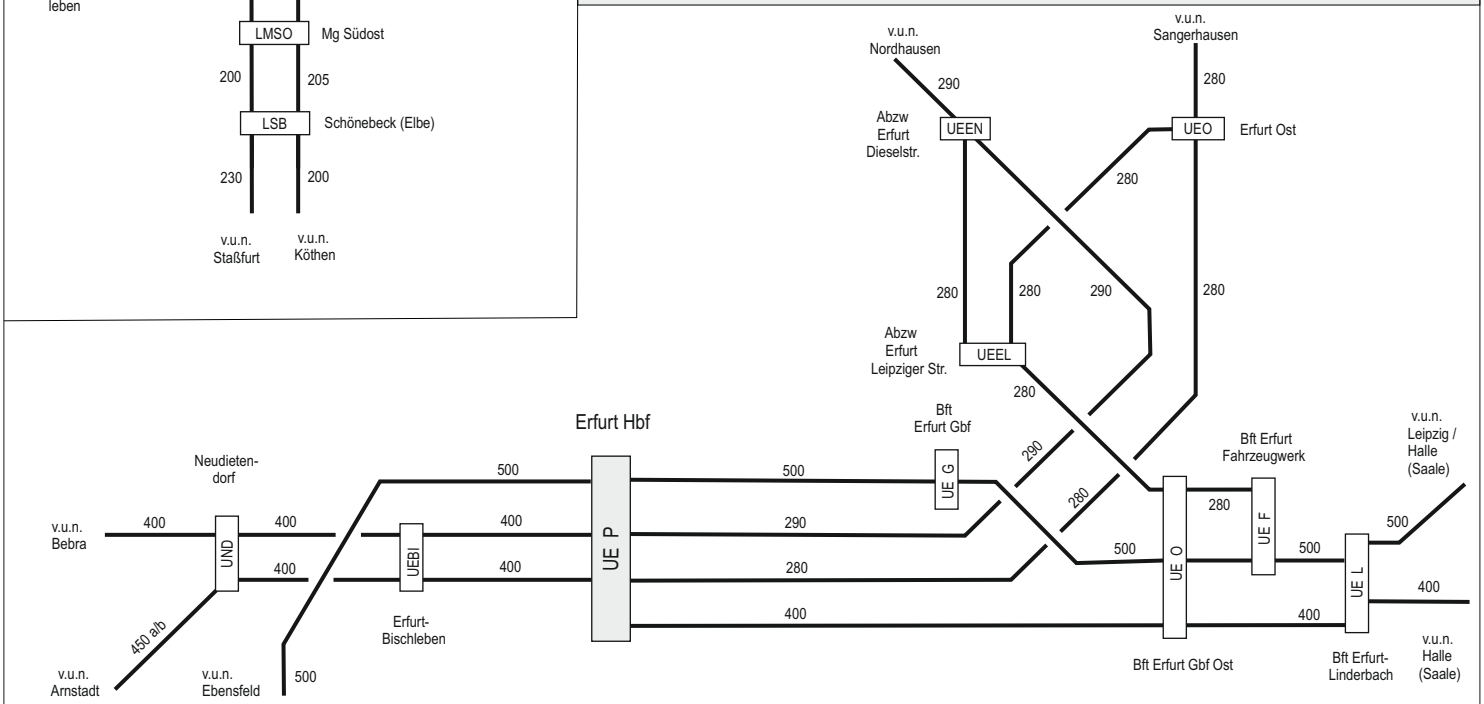

Roßlau

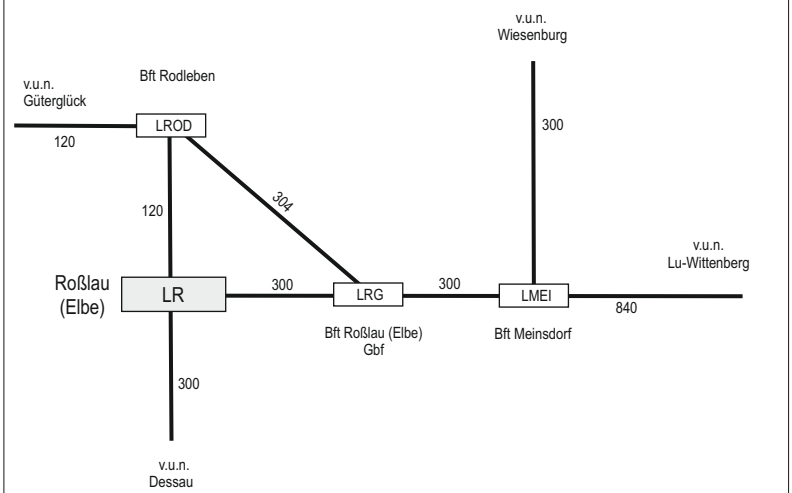

Bitterfeld

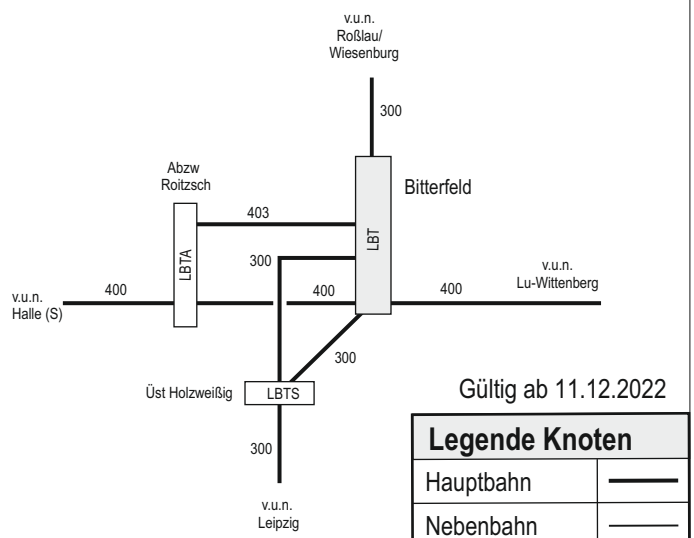

Gültig ab 11.12.2022

Legende Knoten	
Hauptbahn	———
Nebenbahn	———
NE-Bahn	- - - - -